METODOLOGÍA PARA LA DEFINICIÓN DEL NIVEL DE DESARROLLO TURÍSTICO TERRITORIAL

Documento metodológico para la implementación de la herramienta de identificación del nivel de desarrollo turístico territorial

MINISTERIO DE COMERCIO, INDUSTRIA Y TURISMO
VICEMINISTERIO DE TURISMO
2019 – 2021

METODOLOGÍA PARA LA DEFINICIÓN DEL NIVEL DE DESARROLLO TURÍSTICO TERRITORIAL

MINISTERIO DE COMERCIO, INDUSTRIA Y TURISMO
VICEMINISTERIO DE TURISMO

MINISTRO DE COMERCIO, INDUSTRIA Y TURISMO
José Manuel Restrepo Abondano

VICEMINISTRO DE TURISMO
Julián Guerrero Orozco

DIRECTORA DE CALIDAD Y DESARROLLO SOSTENIBLE
Constanza Olaya Cantor

COORDINADORA DE PLANIFICACIÓN Y DESARROLLO SOSTENIBLE
María Eugenia Anzola Tavera

AUTORES

Responsable del proyecto (coordinación y redacción):
Catherine Sánchez Nieto

Equipo de trabajo:
Arturo Bravo (2019 – 2020, ejes oferta y demanda)
Lorena Zapata Villacis (2019 – 2020, ejes oferta y demanda)
Catherine Sánchez Nieto (2019 – 2021 ejes oferta y demanda)
Geraldin Velásquez Vega (2020, ejes oferta y demanda)

Aplicativo:
Alex Fernando Gutiérrez Duarte

Bogotá, Colombia
2019 – 2021

INTRODUCCIÓN

El proceso de desarrollo turístico territorial hace referencia al conjunto de actividades a través de las cuales un destino garantiza la correcta planificación y gestión del territorio, con el fin de prevenir y mitigar los impactos que afecten su desarrollo sostenible. Este proceso debe vincular actores públicos y privados en diferentes escalas y niveles, propiciando la participación de todos los involucrados y la toma de decisiones conjunta para el fortalecimiento de su competitividad turística, dando cumplimiento a las metas y objetivos sectoriales propuestos por el territorio y en coherencia con la realidad del destino.

Debido a la complejidad del sector y entendiendo la importancia de lograr su desarrollo bajo principios de sostenibilidad que permitan la consolidación y comercialización de destinos integrales, el Viceministerio de Turismo, a través del equipo de la Dirección de Calidad y Desarrollo Sostenible del Turismo, pone a disposición de las entidades territoriales de los municipios de Colombia la primera metodología y herramienta tecnológica para la definición del nivel de desarrollo turístico territorial, a través de la cual los 1.103 distritos y municipios del país podrán realizar un ejercicio de autoevaluación a través del cual serán analizados 80 indicadores asociados a 14 ejes de oferta y demanda.

OBJETIVO

Contar con una herramienta metodológica que permita determinar el nivel de desarrollo turístico actual de un destino, a partir de la evaluación y análisis de criterios cuantitativos de oferta y demanda.

OBJETIVOS ESPECÍFICOS

1. Propiciar la toma de decisiones soportada en el análisis de indicadores.
2. Realizar un diagnóstico autónomo desde los gobiernos locales generando conciencia frente al desarrollo turístico territorial, la importancia de la gestión de los gobiernos distritales y municipales y su articulación con los gobiernos departamentales y el nacional.
3. Definir y realizar inversiones de mayor impacto y que respondan de forma real a las necesidades de los destinos y las metas sectoriales.
4. Vincular su desarrollo y resultados al proyecto "Caja de Herramientas para el sector turístico".
5. Motivar a los municipios en la implementación de mediciones y generación de indicadores cuantitativos.

METODOLOGÍA DE EVALUACIÓN

La metodología para la definición del nivel de desarrollo turístico territorial permite realizar una evaluación del momento presente de un destino, identificando así los elementos que requieren mayor atención, gestión o inversión. Para ello, desde el Viceministerio de Turismo fueron estructuradas cinco etapas para la implementación de la metodología, de la siguiente forma:

1. *Ejercicio de autodiagnóstico:*

   En esta etapa, por solicitud de las entidades territoriales, el Viceministerio de Turismo asignará un usuario exclusivo para la implementación de la metodología. El ingreso a la plataforma se hará a través del siguiente portal web http://servicios.mincit.gov.co/turismo_dtt/login.php escribiendo en el espacio "código de municipio" el código DIVIPOLA que le corresponda y una contraseña que será asignada vía correo electrónico.

   En el desarrollo de este ejercicio será fundamental analizar e incorporar la información, datos y otros elementos de parte de los grupos de interés que aporten información al diligenciar la herramienta. Para esto se sugiere realizar sesiones de trabajo en las que se presente, valide, recopile y sistematice la información con el fin de garantizar que esta sea completa y represente a todo el distrito o municipio.

   En esta etapa de implementación, cada uno de los distritos y municipios interesados en la identificación de su nivel de desarrollo turístico, realizará la evaluación de 80 indicadores divididos en siete (7) ejes de oferta y siete (7) de demanda, definidos así:

   OFERTA: (1) Gestión de destinos, (2) Sostenibilidad, (3) Infraestructura, (4) Planta turística, (5) Formación y capacitación, (6) Producto turístico y (7) Promoción y comercialización.

DEMANDA: (1) Demanda nacional, (2) Demanda internacional, (3) Gasto promedio, (4) Ocupación hotelera, (5) Promedio de pernoctación, (6) Presencia digital, (7) Satisfacción de los viajeros.

Para cada uno de los indicadores fueron definidas puntuaciones entre 0 y 10, a través de las cuales se garantiza el cumplimiento efectivo de los criterios. De esta forma, cada entidad territorial tendrá la posibilidad de seleccionar el criterio que se adapte a su realidad, obteniendo un puntaje para cada eje según el porcentaje de relevancia asignado en el proceso de desarrollo turístico territorial en materia de oferta y demanda.

Por así requerirlo y con el fin de entender con mayor profundidad el estado actual de cada indicador, en el proceso de autodiagnóstico serán solicitados un grupo de anexos que puede tener las siguientes características:

a. **DOCUMENTO ADJUNTO:** hace parte de los documentos de trabajo de la autoridad distrital o municipal y valida la respuesta seleccionada en el indicador evaluado.
b. **PLANTILLA:** delimita la información que debe ser suministrada por la autoridad distrital o municipal. Incluye formatos que facilitarán la consolidación, sistematización y análisis de la información. La plantilla tendrá que ser descargada, diligenciada y cargada por la entidad territorial.
c. **CAJA DE INFORMACIÓN:** permite que la autoridad municipal suministre información limitada y específica frente al indicador en evaluación.

Una vez sea finalizado en su totalidad el ejercicio de autodiagnóstico y se hayan diligenciado los soportes correspondientes, el aplicativo tecnológico diseñado para este fin otorgará los resultados realizando el siguiente cálculo:

Promedio de puntaje en el eje 1 x % asignado al eje 1*

*Igual para los 14 ejes

El peso porcentual de cada eje fue asignado de la siguiente forma:

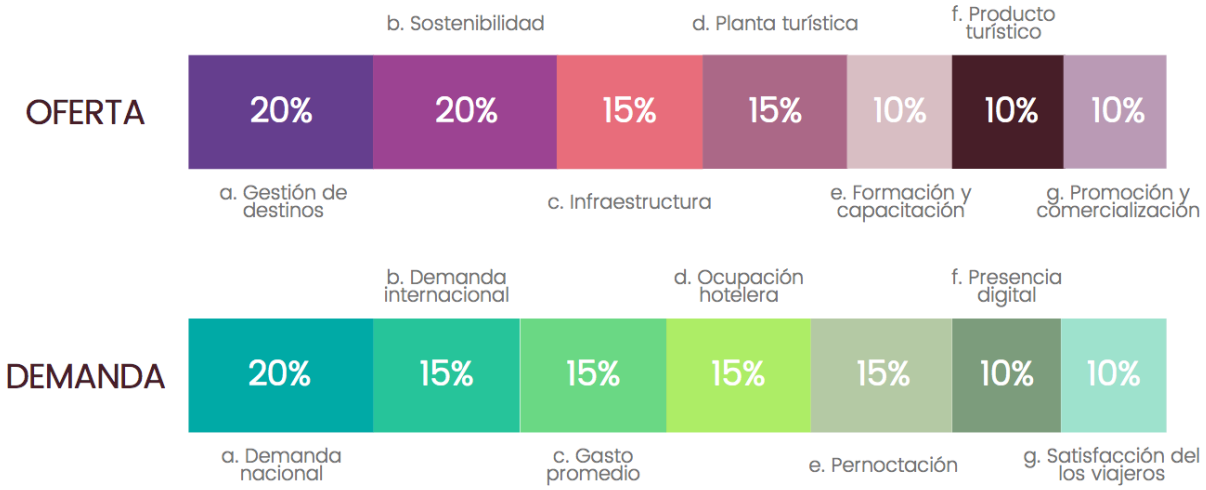

Fuente: elaboración propia, 2020.

Una vez el aplicativo realice la sistematización de las puntuaciones según los porcentajes asignados, este realizará la sumatoria de los resultados en términos oferta y demanda, obteniendo en total dos puntajes que se cruzarán en la siguiente matriz:

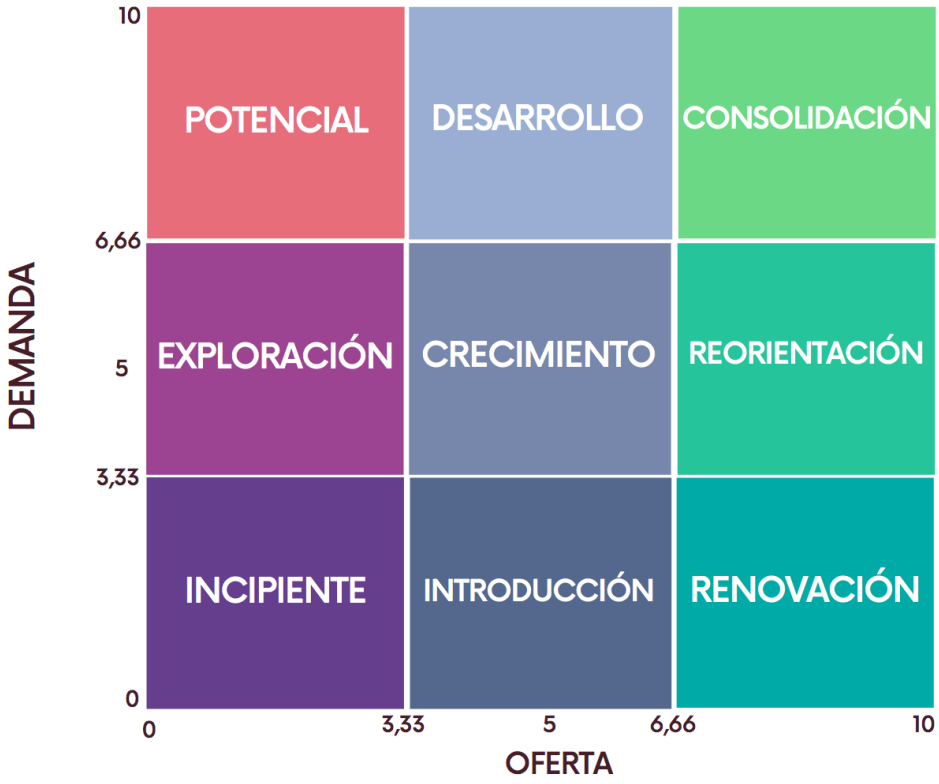

Fuente: elaboración propia, 2020.

Una vez se realice el cruce de la información, el distrito o municipio que implemente la metodología obtendrá el resultado que corresponda según las puntuaciones obtenidas.

A continuación, se presenta un ejemplo del "DESTINO A" con el fin de materializar el resultado del ejercicio:

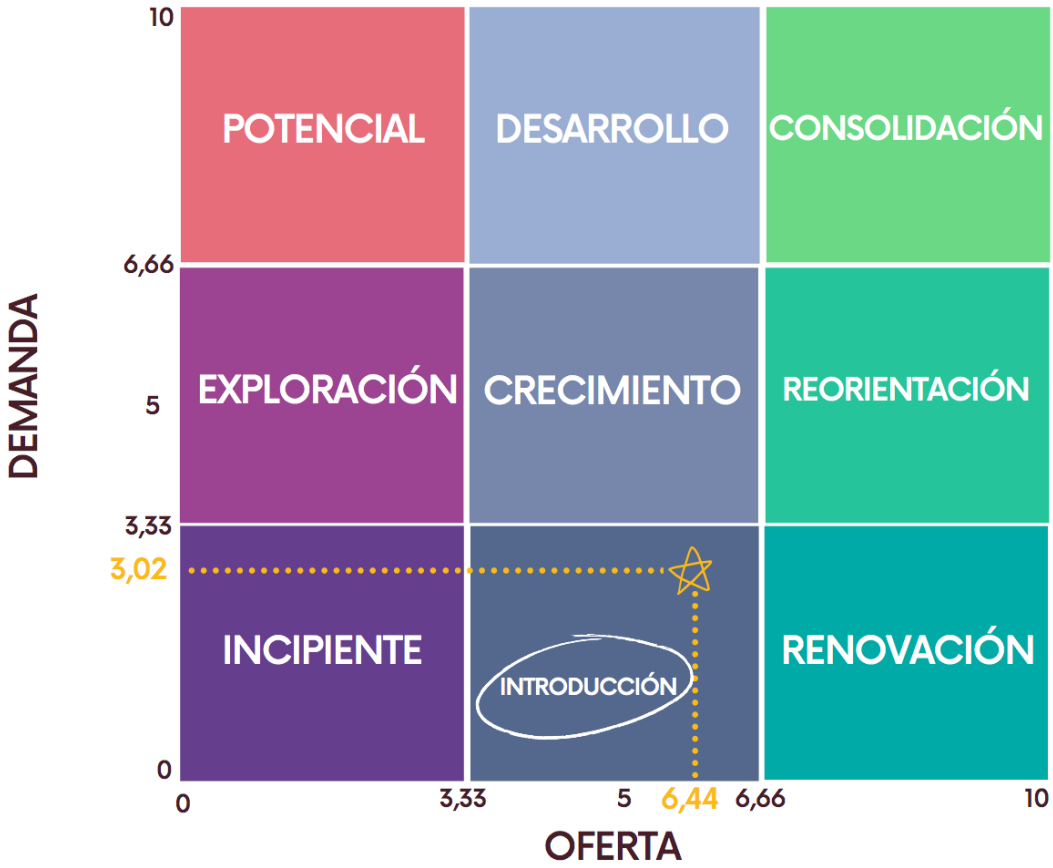

Fuente: elaboración propia, 2020.

En el ejemplo anterior se realiza el cruce de los puntajes obtenidos por el "DESTINO A", a partir de la implementación de la metodología, cuyo resultado le indica que, en este momento, es un destino en fase de "introducción".

A continuación, con el propósito de dar una explicación general de la clasificación resultante, se presentan las definiciones de cada una. *Cabe señalar que las especificidades de las acciones a implementar serán definidas a partir del análisis detallado de cada indicador.*

INCIPIENTE

El destino carece o presenta importantes debilidades en elementos asociados a la oferta del destino, tampoco cuenta con flujos turísticos relevantes; sin embargo, quienes visitan el territorio pueden verse interesados por recursos poco saturados y la autenticidad de las manifestaciones patrimoniales. Es probable que la planta turística sea muy limitada o inexistente y no sea posible garantizar altos estándares de calidad.

EXPLORACIÓN

El destino presenta importantes debilidades en elementos asociados a la oferta del destino; sin embargo, cuenta con algunos flujos turísticos que han adquirido relevancia con el paso del tiempo que se encuentran interesados en atractivos poco intervenidos (probablemente garantizan un viaje económico para el visitante). La planta turística es limitada y es probable que tenga un desarrollo desorganizado o informal.

POTENCIAL

El destino cuenta con importantes flujos turísticos de carácter nacional e internacional que se encuentran interesados en atractivos muy populares y poco intervenidos. La planta turística es limitada y es probable que tenga un desarrollo intuitivo, pero desorganizado o informal. La fuerza laboral destinada para atender la demanda presentará debilidades en la prestación del servicio por carencia de formación e incluso, debido a la alta afluencia de visitantes, es probable que se dé la llegada de actores externos al municipio para suplir algunas necesidades. La planta turística es insuficiente y con importantes debilidades en materia de calidad.

INTRODUCCIÓN

El destino cuenta con una oferta turística que avanza en el proceso de gestión de destino a través de la articulación con los actores del sector; quienes entienden el potencial del destino y se han preparado para habilitar la llegada ordenada de turistas. Es posible identificar iniciativas de base comunitaria que se encuentran interesadas en poner en valor el patrimonio natural y cultural del destino.

Cuenta con escasos flujos turísticos que pueden no encontrar interés en el destino debido a dificultades de acceso o seguridad. La planta turística puede ser aún insuficiente y no contar con criterios de formalización o calidad. El destino se encuentra priorizando inversiones en infraestructura que fortalezcan la calidad de la experiencia turística.

CRECIMIENTO

El flujo de turistas ha incrementado con el tiempo gracias a los esfuerzos del destino por fortalecer los componentes que integran su oferta turística e inversiones en promoción. La planta turística se encuentra en proceso de formalización e implementación de criterios de calidad que le permitan atraer visitantes de nuevos perfiles.

Empresarios encuentran en el destino la posibilidad de realizar inversiones y beneficiarse económicamente. Las comunidades locales y sus iniciativas perciben los beneficios de la llegada de un mayor número de turistas y reconocen la importancia de contar con fuerza laboral que tenga la capacidad de atender nuevos perfiles de visitantes.

DESARROLLO

El destino cuenta con una oferta turística en proceso de fortalecimiento o estancada. Los actores involucrados en el desarrollo de la actividad reconocen el potencial del destino y comprenden la importancia de mejorar para ofrecer una experiencia ordenada y de calidad.

Cuenta con importantes flujos turísticos de carácter nacional e internacional, que pueden visitar estos destinos por considerarse "puntos de encuentro o de partida" hacia otros destinos, sin embargo, su oferta no satisface algunas de las motivaciones de los turistas. Algunos de los destinos clasificados en esta categoría pueden estar pasando por una etapa de saturación que afecta su organización y avance; la actividad turística puede estar generando efectos negativos en la sostenibilidad del destino.

RENOVACIÓN

El destino cuenta con un buen desarrollo de los criterios que integran la oferta turística. La planta turística es variada y tiene la capacidad para atender a un importante número de personas. Cuenta con fuerza laboral capacitada para recibir turistas nacionales e internacionales y condiciones de infraestructura óptimas.

Es probable que los flujos turísticos hayan disminuido (perdido interés en el destino) y la dinámica turística se haya desacelerado. Por otra parte, puede que, a pesar del trabajo sobre el eje de oferta, estos esfuerzos se hayan dirigido de forma equivocada hacia productos, campañas de promoción u otras acciones que no atienden a los flujos reales del destino.

REORIENTACIÓN

La oferta turística del destino se encuentra en un buen nivel de desarrollo, sin embargo, la llegada de visitantes se encuentra estancada y los esfuerzos para atraer nuevos turistas no tienen una respuesta extraordinaria.

El destino se ve afectado por los impactos de la actividad y puede darse un fenómeno de sobreoferta, por lo que puede tener problemas para alcanzar altos niveles de ocupación, afectando el ingreso de los inversionistas.

CONSOLIDACIÓN

El destino cuenta con niveles destacados en el desarrollo de la oferta y recibe un importante número de turistas nacionales e internacionales que se mantiene en el tiempo. El destino identifica afectaciones por uso sobre las infraestructuras y planta turística, así como impactos que pueden perjudicar la sostenibilidad del destino (mayor número de turistas frente al número de residentes, impactos en la disponibilidad de servicios básicos, contaminación, daño del patrimonio, inseguridad, aculturación, delitos, entre otros).

Por lo general, un importante porcentaje del destino recibe ingresos y se beneficia casi exclusivamente del turismo. Pueden presentarse escenarios de rechazo a la actividad turística, razón por la cual la gestión distrital o municipal

tendrá que orientar sus esfuerzos hacia el equilibrio entre la actividad y el bienestar de las comunidades de destino.

Una vez obtenida la puntuación y la clasificación del distrito o municipio, se da por finalizada la etapa de autodiagnóstico.

2. *Análisis de resultados y verificación de anexos por municipio.*

Una vez ejecutado el ejercicio de autodiagnóstico, el equipo del Viceministerio de Turismo realizará un ejercicio de análisis de las respuestas y verificación de los anexos incluidos en la herramienta.

En caso de que el Viceministerio de Turismo tenga observaciones frente a los anexos o respuestas, se contactará directamente con el contacto vinculado a la plataforma con el fin de revisar y aclarar posibles inquietudes.

3. *Estructuración del plan de trabajo y socialización*

Una vez el equipo del Viceministerio de Turismo haya realizado el análisis de la información que corresponda, procederá a estructurar un documento preliminar de acciones a corto plazo (un año) que deben ser de inmediata implementación para avanzar en el proceso de desarrollo turístico. Así mismo, se presentarán recomendaciones que deben iniciar un proceso de implementación para obtener resultados a mediano o largo plazo; lo anterior permitirá avanzar en simultáneo en múltiples frentes que permitirán su evolución.

Una vez el Viceministerio de Turismo cuente con el documento preliminar, se realizará una jornada de socialización y estructuración conjunta del plan de trabajo, el cual será validado y aprobado por los presentes (autoridades de turismo o responsables de esta cartera, representantes de los prestadores de servicios turísticos, comunidades de destino y otras entidades o actores que se consideren relevantes en el desarrollo de la actividad turística municipal). Se estructurará un cronograma de trabajo con el fin de trazar objetivos y realizar seguimiento.

4. *Ejecución y seguimiento de las acciones propuestas.*

   Una vez se obtenga el plan de trabajo aprobado por las partes, los actores responsables de la ejecución de las actividades propuestas iniciarán su ejecución. Con el fin de realizar un seguimiento sobre las acciones para apoyar posibles dificultades que se presenten en el proceso, el equipo del Viceministerio de Turismo realizará un seguimiento mensual de las actividades que será consolidado en el sistema dispuesto para el ejercicio de autoevaluación.

5. *Evaluación de cumplimiento y nuevo autodiagnóstico.*

   Al finalizar cada vigencia anual y según el seguimiento realizado por el equipo del Viceministerio de Turismo, se realizará una evaluación de las actividades propuestas con el fin de validar su ejecución y resultado. El ejercicio final será socializado a la entidad territorial y posterior a ello, se procederá a realizar nuevamente la evaluación con el fin de subsanar o ajustar los puntajes en los que se presenten avances para el desarrollo turístico territorial e iniciar nuevamente el proceso de planeación anual.

INDICADORES Y CALIFICACIÓN

A continuación, se describen los 80 indicadores que conforman el ejercicio de autodiagnóstico y para los cuales se estructuraron definiciones que facilitarán su comprensión, así como criterios de calificación que delimitan las puntuaciones.

Cada indicador se encuentra conformado por los elementos que se presentan en el siguiente ejemplo:

1. OFERTA

Gestión de destinos

Turismo en el plan de desarrollo: como herramienta de gestión pública y desarrollo social, este plan determina las bases para atender necesidades territoriales que, una vez sean resueltas, permitan mejorar la calidad de vida de la comunidad que habita un territorio. Para lograr un puntaje positivo en este criterio, la actividad turística debe ser incluida en el plan de desarrollo del distrito o municipio, entendiendo que a partir de ello se destinan recursos (humanos, físicos y financieros) para el fortalecimiento del sector, posibilitando además el acceso a la oferta institucional y recursos del Viceministerio de Turismo administrados a través del FONTUR.

CRITERIOS	PUNTAJE
El Plan de Desarrollo distrital o municipal INCLUYE a la actividad turística como una línea estratégica que se desarrollará a través de proyectos y programas que cuentan con un plan de inversión.	10
El Plan de Desarrollo distrital o municipal incluye a la actividad turística de manera general. No determina programas y proyectos que respalden el fortalecimiento de la actividad turística.	5
El Plan de Desarrollo distrital o municipal NO incluye a la actividad turística.	0

Nota: para esta metodología se evaluará el criterio a nivel distrital o municipal.

Fuente de consulta: Plan de Desarrollo Turístico municipal o documentación oficial de la alcaldía municipal.

Anexo: documento que corresponda al plan de desarrollo del distrito o municipio.

Fuente: elaboración propia, 2020.

- Ordinal: hace referencia al número del indicador.
- Grupo: clasifica los indicadores en el grupo que corresponda según sus características (oferta o demanda).
- Eje: responde a uno de los 14 ejes definidos en la metodología y en el que se encuentra clasificado cada indicador.
- Título del indicador: nombre asignado a cada indicador que informa de manera rápida el tema a evaluar.
- Descripción: explica de forma breve a qué hace referencia el indicador.
- Criterios: opciones de evaluación que quien realice la evaluación tendrá la posibilidad de seleccionar, según corresponda para su destino.
- Puntaje: hace referencia a los puntajes asignados a cada criterio, que serán otorgados a cada indicador según lo considere el distrito o municipio.
- Nota: describe brevemente el anexo que debe ser vinculado a la herramienta como corresponda (no todos los indicadores requieren un anexo).
- Fuente de consulta: indica cuál será el documento o herramienta de consulta para cada indicador. En un grupo de indicadores se adjunta el documento de consulta con el fin de estandarizar el ejercicio de evaluación.
- Anexo: hace referencia al soporte que para algunos indicadores deben ser cargados o diligenciados en la plataforma.

Nota: algunas de los puntajes máximos no indican que el distrito o municipio esté en el nivel ideal, sino que para el contexto actual pueden estar mejor calificados que otros o están más cerca del máximo de evaluación (máximos y mínimos).

OFERTA

EJE 1
GESTIÓN DE DESTINO

La gestión de destinos entiende el territorio como una organización que integra y articula a todos los actores que tienen responsabilidades y compromisos en el desarrollo turístico, con quienes se realiza la coordinación de actividades para el beneficio del destino y la optimización de recursos disponibles (Ministerio de Comercio, Industria y Turismo, 2019).

Este eje permite evaluar elementos que deben ser priorizados en el desarrollo turístico territorial, pues se constituyen como parte esencial de los procesos de gobernanza, articulación interinstitucional y planificación turística. Alcanzar un puntaje destacado en estos criterios indicará que el distrito o municipio cuenta con las bases necesarias para el desarrollo territorial, validando la importancia de la actividad turística en el mismo.

1. **Turismo en el Plan de Desarrollo distrital o municipal:** como herramienta de gestión pública y desarrollo social, este plan determina las bases para atender necesidades territoriales que, una vez sean resueltas, permitan mejorar la calidad de vida de la comunidad que habita un territorio. Para lograr un puntaje positivo en este criterio, la actividad turística debe ser incluida en el plan de desarrollo del distrito o municipio, entendiendo que a partir de ello se destinan recursos (humanos, físicos y financieros) para el fortalecimiento del sector, posibilitando además el acceso a la oferta institucional y recursos del Viceministerio de Turismo administrados a través del FONTUR.

Evaluación

CRITERIO	PUNTAJE
El Plan de Desarrollo distrital o municipal **INCLUYE** a la actividad turística como una línea estratégica que se desarrollará a través de proyectos y programas que cuentan con un plan de inversión.	10
El Plan de Desarrollo distrital o municipal incluye a la actividad turística de manera general. No determina programas y proyectos que respalden el fortalecimiento de la actividad turística.	5
El Plan de Desarrollo distrital o municipal **NO** incluye a la actividad turística.	0

Fuente de consulta: *plan de desarrollo distrital o municipal aprobado por el Concejo Municipal.*
Anexo: *documento del plan de desarrollo del distrito o municipio.*

2. **Plan de desarrollo turístico:** herramienta de planificación turística que incluye los lineamientos necesarios para la gestión de un territorio, a través de la formulación de estrategias y la definición de acciones que orientan el desarrollo turístico distrital o municipal bajo principios de competitividad y sostenibilidad, atendiendo las directrices del Plan de Desarrollo distrital o municipal.

Evaluación

CRITERIO	PUNTAJE
SÍ cuenta con Plan de Desarrollo Turístico distrital o municipal vigente*	10
Cuenta con un documento similar a un plan de trabajo, que incluye las orientaciones para el desarrollo turístico distrital o municipal*	5
NO cuenta con Plan de Desarrollo Turístico distrital o municipal vigente*	0

**Para esta metodología el indicador se evaluará a nivel distrital o municipal.*
1. El documento debe corresponder al periodo de gobierno de la administración actual.

Fuente de consulta: *plan de desarrollo turístico distrital o municipal o documentación oficial de la alcaldía municipal.*
Anexo: *documento plan de desarrollo turístico (10) o documento similar (5).*

3. **Oficina para la gestión turística:** entidad, organismo o dependencia distrital o municipal encargada de planear y ejecutar acciones que contribuyan al fomento y desarrollo turístico territorial.

Evaluación

CRITERIO	PUNTAJE
El distrito o municipio **SÍ** cuenta con una entidad, organismo o dependencia especializada en gestión turística*.	10
El distrito o municipio **NO** cuenta con una entidad, organismo o dependencia especializada en gestión turística.	0

1. La dependencia de turismo podrá estar vinculada con otras áreas que el gobierno distrital o municipal haya considerado estratégico agrupar. Ej. Secretaría de Cultura y Turismo.

Fuente de consulta: *documento normativo que evidencie la creación de la oficina, entidad, organismo o dependencia especializada en gestión turística.*
Anexo: *documento normativo a través del cual se crea la oficina o dependencia de turismo.*

4. **Presupuesto destinado al turismo:** recursos del presupuesto distrital o municipal destinados al funcionamiento de la oficina de turismo o el desarrollo de proyectos que contribuyan al fortalecimiento de la competitividad y promoción turística.

Evaluación

CRITERIO	PUNTAJE
El distrito o municipio **SÍ** cuenta con recursos presupuestales destinados a la actividad turística.	10
El distrito o municipio **NO** cuenta con recursos presupuestales destinados a la actividad turística.	0

Fuente de consulta: *plan de desarrollo distrital o municipal. Plan Anual de Adquisiciones del distrito o municipio.*
Cuadro de información: *monto presupuestal del año en el que se implementa la metodología. Incluir el valor con todos los dígitos sin el signo pesos. En caso de seleccionar el criterio "El distrito o municipio NO cuenta con recursos presupuestales destinados a la actividad turística", escriba 0.*

5. **Consejo distrital o municipal de turismo:** organismo distrital o municipal, que cumple las mismas funciones del Consejo Consultivo de la Industria Turística en el ámbito de sus competencias territoriales (Ley 1558, 2012).

Evaluación

CRITERIO	PUNTAJE
El distrito o municipio **SÍ** cuenta con un consejo distrital o municipal de turismo.	10
El distrito o municipio hace parte de una mesa de turismo u otro mecanismo de articulación regional, departamental, distrital o municipal.	5
El distrito o municipio **NO** cuenta con consejo distrital o municipal, ni hace parte de una mesa de turismo u otro mecanismo de articulación regional, departamental, distrital o municipal.	0

Fuente de consulta: *documentación oficial de la alcaldía distrital o municipal.*
Anexo: *documento que soporte la conformación de un Consejo de Turismo, distrital o municipal según sea el caso.*

6. **Articulación* del municipio (sector turismo) con la Comisión Regional de Competitividad e Innovación:** las comisiones regionales de competitividad e innovación son las "encargadas de la coordinación y articulación de las distintas instancias a nivel departamental y subregional que desarrollen actividades dirigidas a fortalecer la competitividad e innovación en los departamentos en el marco del Sistema Nacional de Competitividad e Innovación. (...) son un espacio para la cooperación público - privada y académica a nivel departamental, orientada a la implementación de las Agendas Departamentales de Competitividad e Innovación" (Decreto 1651, 2019).

Evaluación

CRITERIO	PUNTAJE
La autoridad de turismo del municipio o distrito **SÍ** se articula en la Comisión Regional de Competitividad e Innovación de su departamento.	10
La autoridad de turismo del municipio o distrito **NO** se articula con la Comisión Regional de Competitividad e Innovación de su departamento.	0

1. Se entenderá como articulación, la comunicación permanente y fluida de los representantes del sector turístico del distrito o municipio, con los integrantes de la respectiva Comisión Regional de Competitividad.

Fuente de consulta: *documentación oficial de la alcaldía municipal.*
Anexo plantilla: *documento que da cuenta de las acciones de articulación con la Comisión Regional de Competitividad e Innovación.*

7. **Participación del distrito o municipio (sector turismo) en un clúster de turismo regional, departamental o municipal:** el concepto de clúster hace referencia a "la concentración de empresas, proveedores especializados, proveedores de servicios, compañías en industrias relacionadas e instituciones de apoyo (como, por ejemplo, universidades, centros de desarrollo tecnológico, centros de investigación, agencias regulatorias, gremios, etc.) en una misma región geográfica, que se desempeñan en las mismas actividades o en actividades estrechamente relacionadas"

(iNNpulsa, 2020). Para este caso se evaluarán los clústeres existentes para el sector turismo.

Evaluación

CRITERIO	PUNTAJE
El sector turístico del distrito o municipio **SÍ** participa en un clúster de turismo regional, departamental o municipal.	10
El sector turístico del distrito o municipio **NO** participa en un clúster de turismo regional, departamental o municipal; pero sus empresarios se encuentran vinculados a asociaciones turísticas.	5
El sector turístico del distrito o municipio **NO** participa en un clúster de turismo regional, departamental o municipal.	0

Fuente de consulta: *documentación oficial de la alcaldía municipal.*
Anexo plantilla: *documento que identifica los clústeres de turismo y las asociaciones turísticas en el distrito o municipio y sus principales acciones.*

8. **Plan de trabajo de articulación público - privada:** herramienta empleada para la sistematización y seguimiento de acciones cuya ejecución es propuesta para cada vigencia anual. El documento es construido de forma conjunta, con la participación de actores públicos y privados de los distritos o municipios que conforman la estrategia de Gestión Integral de Destinos del Viceministerio de Turismo.

Evaluación

CRITERIO	PUNTAJE
El distrito o municipio **SÍ** hace parte de la estrategia de Gestión Integral de Destinos y hace parte del plan de trabajo de articulación público – privada.	10
El distrito o municipio **NO** hace parte de la estrategia de Gestión Integral de Destinos y no hace parte del plan de trabajo de articulación público – privada.	0

Fuente de consulta: *Viceministerio de Turismo (municipios en la estrategia de Corredores Turísticos).*

9. **Posición del departamento al que pertenece el distrito o municipio en el Índice de Competitividad Turística Regional de Colombia (ICTRC), departamentos:** este índice permite registrar y medir los factores asociados a la competitividad turística departamental.

Evaluación

CRITERIO	PUNTAJE
El departamento se encuentra en el **Grupo 1** de la calcificación departamental en el ICTRC (departamentos con ICTRC entre 7,1 y 6,0).	10
El departamento se encuentra en el **Grupo 2** de la calcificación departamental en el ICTRC (departamentos con ICTRC entre 5,6 y 5,0).	8
El departamento se encuentra en el **Grupo 3** de la calcificación departamental en el ICTRC (departamentos con ICTRC entre 4,8 y 3,9).	6
El departamento se encuentra en el **Grupo 4** de la calcificación departamental en el ICTRC (departamentos con ICTRC entre 3,6 y 2,6).	4
El departamento **NO** se encuentra la clasificación departamental del ICTRC.	2

1. Ver página 88 del documento de consulta.

***Fuente de consulta:** Índice de Competitividad Turística Regional de Colombia, Centro de Pensamiento Turístico Colombia (departamentos) del año anterior al que se implemente la metodología. Ver página 88 del documento de consulta.*

10. Posición del municipio o ciudad capital en el Índice de Competitividad Turística Regional de Colombia (ICTRC), ciudades capitales y municipios: este índice permite registrar y medir los factores asociados a la competitividad turística de ciudades capitales y municipios.

Evaluación

CRITERIO	PUNTAJE
La ciudad capital o municipio dentro del ranking de ICTRC obtuvo un puntaje mayor que **8,01 y hasta 10.**	10
La ciudad capital o municipio dentro del ranking de ICTRC obtuvo un puntaje mayor que **6,01 y hasta 8,00.**	8
La ciudad capital o municipio dentro del ranking de ICTRC obtuvo un puntaje mayor que **4,01 y hasta 6,00.**	6
La ciudad capital o municipio dentro del ranking de ICTRC obtuvo un puntaje mayor que **2,01 y hasta 4,00.**	4
La ciudad capital o municipio dentro del ranking de ICTRC obtuvo un puntaje mayor que **0 y hasta 2,00.**	2
El municipio **NO** se encuentra en la clasificación de ciudades capitales y municipios del ICTRC.	0

1. Ver páginas 8 (ciudades capitales) y 103 y 104 (municipios) del documento de consulta.

***Fuente de consulta:** Índice de Competitividad Turística Regional de Colombia, Centro de Pensamiento Turístico Colombia (ciudades capitales y municipios) del año anterior al que se implemente la metodología.*

EVALUACIÓN DEL EJE GESTIÓN DE DESTINOS (20%)

Como resultado de la evaluación de los indicadores previamente descritos, se generará un puntaje para el eje "Gestión de destinos" que será calculado realizando la división de la sumatoria del total de los criterios ya evaluados en el eje en el número total de criterios, que para este caso es **10**. El resultado será multiplicado por **20%** que corresponde al peso porcentual del eje sobre el componente de oferta.

EJE 2
ASPECTOS ASOCIADOS A LA SOSTENIBILIDAD TURÍSTICA

Por su dinámica, la actividad turística genera impactos ambientales, culturales, sociales y económicos que pueden ser positivos o negativos según como se adelanten los procesos de planificación turística, apropiación del territorio, articulación y corresponsabilidad, formalización, sensibilización, entre otros. Por lo anterior, teniendo en cuenta la importancia que para el sector representa adelantar acciones que contribuyan a la generación de ingresos y empleo, el aumento de la capacidad empresarial, la distribución de ingresos, la contribución al Producto Interno Bruto (PIB), el efecto multiplicador, la diversificación económica, la preservación del patrimonio natural y cultural (material e inmaterial) y al mejoramiento de la calidad de vida de las comunidades de destino; se hace necesario implementar acciones permanentes que garanticen la sostenibilidad de la actividad turística en cualquier territorio.

11. **Nivel de satisfacción de la comunidad local con el turismo*:** "abarca aspectos reales y aspectos que dependen de la percepción, como la masificación, el acceso a puestos de trabajo, la participación en los beneficios, la reacción ante el comportamiento de los turistas" (OMT, 2005), entre otros asuntos relevantes para el bienestar de las comunidades de destino.

Evaluación

CRITERIO	PUNTAJE
El distrito o municipio **SÍ** registra **Y** gestiona de forma oportuna las peticiones, quejas, reclamaciones, sugerencias y felicitaciones presentadas por la comunidad local, asociadas a la actividad turística.	10
El distrito o municipio **SÍ** registra las peticiones, quejas, reclamaciones, sugerencias y felicitaciones presentadas por la comunidad local, asociadas a la actividad turística, pero no realiza gestiones oportunas para su atención.	5
El distrito o municipio **NO** cuenta con un registro de peticiones, quejas, reclamaciones, sugerencias y felicitaciones presentadas por la comunidad local, asociadas a la actividad turística.	0

**Para este indicador se tomará como base de información el registro de peticiones, quejas, reclamaciones, sugerencias o felicitaciones presentadas por la comunidad local.*

1. En futuros ejercicios el Viceministerio de Turismo solicitará que el distrito o municipio genere información detallada de las peticiones, quejas, reclamaciones, sugerencias o felicitaciones presentadas por la comunidad local.

Fuente de consulta: *documentación oficial de la alcaldía distrital o municipal: registro de peticiones, quejas, reclamaciones, sugerencias o felicitaciones (encuestas o registro oficial de la alcaldía) presentadas por la comunidad local.*

Cuadro de información: *incluir el número de peticiones, quejas, reclamaciones, sugerencias o felicitaciones presentadas por la comunidad local en el año anterior a la implementación de esta metodología (enero - diciembre de 2020).*

12. **Explotación Sexual Comercial de Niños, Niñas y Adolescentes (ESCNNA) en el contexto de viajes y turismo:** hace referencia a la "violación de los derechos fundamentales de la niñez y es considerada por la legislación colombiana

como un delito, en el cual una o más personas denominadas proxenetas, utilizan a hombres o mujeres menores de 18 años (denominadas víctimas), para realizar actividades sexuales, eróticas o de pornografía con el objeto de satisfacer los intereses o deseos de un tercero (denominado abusador) a cambio de un pago o promesa de pago, el cual puede ser en efectivo, en especie o en cualquier otro tipo de participación económica para la víctima y/o el proxeneta" (Ministerio de Comercio, Industria y Turismo, 2015).

Evaluación

CRITERIO	PUNTAJE
En el distrito o municipio **NO** se presentan casos asociados a la vulneración de los derechos de los niños, niñas y adolescentes por ESCNNA en el contexto de viajes y turismo **Y** cuenta con una estrategia de prevención del delito, en ejecución.	10
El distrito o municipio **SÍ** registra **Y** gestiona de forma oportuna los casos de vulneración de los derechos de los niños, niñas y adolescentes por ESCNNA en el contexto de viajes y turismo a través de una estrategia de mitigación del delito.	8
El distrito o municipio **SÍ** registra, pero **NO** gestiona de forma oportuna los casos de vulneración de los derechos de los niños, niñas y adolescentes por ESCNNA en el contexto de viajes y turismo, por no contar con una estrategia de mitigación del delito.	2
El distrito o municipio **NO** cuenta con una herramienta de registro de los casos de vulneración de los derechos de los niños, niñas y adolescentes por ESCNNA en el contexto de viajes y turismo.	0

Fuente de consulta: *documentación oficial de la alcaldía distrital o municipal.*
Anexo*: en caso de que el distrito o municipio seleccione los criterios 10 u 8, deberá adjuntar el documento que presente la estrategia de prevención o mitigación de la ESCNNA en el contexto de viajes y turismo y los resultados de su desarrollo.*

13. **Obstáculos económicos en el acceso a actividades turísticas para la población local:** cuando para acceder a una actividad o atractivo turístico se establece una tarifa de entrada que representa un obstáculo para la población local. Teniendo en cuenta que a menudo las tarifas se establecen en función de la capacidad adquisitiva de los visitantes, en algunos destinos un precio elevado puede excluir a los residentes (OMT, 2005).

Evaluación:

CRITERIO	PUNTAJE
El distrito o municipio, prestadores de servicios y administradores de atractivos turísticos **SI** cuentan con tarifas diferenciales para el acceso de la población local.	10
El distrito o municipio, prestadores de servicios y administradores de atractivos turísticos **NO** cuentan con tarifas diferenciales para el acceso de la población local.	0

1. Este indicador tendrá en cuenta únicamente aquellos atractivos que generan cobro para su ingreso y uso.

Fuente de consulta: *documentación oficial de la alcaldía municipal o distrital.*
Anexo plantilla: *lista de atractivos o actividades turísticas con tarifas preferenciales para la comunidad local, incluyendo tarifas y beneficiarios.*

14. **Lineamientos de accesibilidad para el sector turístico:** hace referencia a las "condiciones, medidas y acciones afirmativas que deben cumplir las instalaciones y los servicios de información para adaptar el entorno, productos y servicios, así como los objetos, herramientas y utensilios, con el fin de asegurar el acceso de las personas con discapacidad" a actividades y atractivos turísticos (Ley Estatuaria 1618 de 2013).

Evaluación:

CRITERIO	PUNTAJE
El distrito o municipio cuenta con un plan de accesibilidad vigente, específico para el sector turismo.	10
El distrito o municipio **SI** contempla aspectos de accesibilidad para el sector turismo, inmersos en un documento formal (plan de acción distrital o municipal).	5
El distrito o municipio **NO** contempla aspectos de accesibilidad para el sector turismo, inmersos en un documento formal (plan de acción distrital o municipal).	0

Fuente de consulta: *documentación oficial de la alcaldía distrital o municipal.*
Anexo: *plan de accesibilidad o documento que incluya aspectos asociados a la accesibilidad turística en el distrito o municipio.*

15. **Informalidad laboral asociada a la actividad turística*:** "incluye todo trabajo remunerado (p.ej. tanto autoempleo como empleo asalariado) que no está registrado, regulado o protegido por marcos legales o normativos, así como también trabajo no remunerado llevado a cabo en una empresa generadora de ingresos. Los trabajadores informales no cuentan con contratos de empleo seguros, prestaciones laborales, protección social o representación de los trabajadores" (Organización Internacional del Trabajo, 2020).

Evaluación

CRITERIO	PUNTAJE
El puntaje para el indicador de "informalidad laboral" incluido en el Índice de Competitividad Turística de Colombia (departamentos) **está entre 8.01 y hasta 10.**	10
El puntaje para el indicador de "informalidad laboral" incluido en el Índice de Competitividad Turística de Colombia (departamentos) **está entre 6.01 y hasta 8.**	8
El puntaje para el indicador de "informalidad laboral" incluido en el Índice de Competitividad Turística de Colombia (departamentos) **está entre 4.01 y hasta 6.**	6
El puntaje para el indicador de "informalidad laboral" incluido en el Índice de Competitividad Turística de Colombia (departamentos) **está entre 2.01 y hasta 4.**	4
El puntaje para el indicador de "informalidad laboral" incluido en el Índice de Competitividad Turística de Colombia (departamentos) **es mayor que 0 y hasta 2.**	2
El puntaje para el indicador de "informalidad laboral" incluido en el Índice de Competitividad Turística de Colombia (departamentos) **es igual a 0.**	0

**Para este indicador se tomará la medición a nivel departamental.*

Fuente de consulta: *Índice de Competitividad Turística Regional de Colombia, (departamentos) del año anterior al que se implemente la metodología. Ver puntaje indicador "informalidad laboral".*

16. **Salarios en el sector turístico*:** remuneración económica que perciben las personas empleadas en las actividades del sector turístico.

Evaluación

CRITERIO	PUNTAJE
El puntaje para el indicador de "salario del sector turismo" incluido en el Índice de Competitividad Turística de Colombia (departamentos) **está entre 8.01 y 10.**	10
El puntaje para el indicador de "salario del sector turismo" incluido en el Índice de Competitividad Turística de Colombia (departamentos) **está entre 6.01 y 8.**	8
El puntaje para el indicador de "salario del sector turismo" incluido en el Índice de Competitividad Turística de Colombia (departamentos) **está entre 4.01 y 6.**	6
El puntaje para el indicador de "salario del sector turismo" incluido en el Índice de Competitividad Turística de Colombia (departamentos) **está entre 2.01 y 4.**	4
El puntaje para el indicador de "salario del sector turismo" incluido en el Índice de Competitividad Turística de Colombia (departamentos) **es mayor que 0 y hasta 2.**	2
El puntaje para el indicador de "salario del sector turismo" incluido en el Índice de Competitividad Turística de Colombia (departamentos) **es igual a 0.**	0

**Para este indicador se tomará la medición a nivel departamental.*

Fuente de consulta: *Índice de Competitividad Turística Regional de Colombia (departamentos) del año anterior al que se implemente la metodología. Indicador "Salario del sector turístico".*

17. **Tráfico de fauna y flora:** "actividades ilícitas de aprovechamiento, movilización, tenencia, uso y comercio de especímenes silvestres (organismos de la diversidad biológica, vivos o muertos o cualquier parte, producto o derivado)" (Policía Nacional, 2017).

Evaluación

CRITERIO	PUNTAJE
En el distrito o municipio **NO** se presentan casos asociados al delito de tráfico de fauna y flora en el contexto de viajes y turismo **Y** cuenta con una estrategia de prevención del delito, en ejecución.	10
El distrito o municipio **SÍ** registra **Y** gestiona de forma oportuna los casos de tráfico de fauna y flora en el contexto de viajes y turismo a través de una estrategia de mitigación del delito.	8
El distrito o municipio **SÍ** registra, pero **NO** gestiona de forma oportuna los casos de tráfico de fauna y flora en el contexto de viajes y turismo, por no contar con una estrategia de mitigación del delito.	2
El distrito o municipio **NO** cuenta con una herramienta de registro de los casos de tráfico de fauna y flora en el contexto de viajes y turismo.	0

Fuente de consulta: *documentación oficial de la alcaldía municipal o distrital.*
Anexo: *en caso de que el distrito o municipio seleccione los criterios 10 u 8, deberá adjuntar el documento que presente la estrategia de prevención o mitigación del tráfico de fauna y flora en el contexto de viajes y turismo y los resultados de su desarrollo.*

18. **Preservación, salvaguardia o promoción del patrimonio cultural:** hace referencia a la medición de iniciativas o empresas cuyas actividades se encuentran asociadas a la preservación, salvaguardia o promoción del patrimonio cultural (artesanías, gastronomía, artes y oficios, medicina tradicional, tradición oral, danza, entre otros) del distrito o municipio.

Evaluación

CRITERIO	PUNTAJE
El distrito o municipio **SÍ** cuenta con iniciativas o empresas cuyas actividades se encuentren asociadas a la preservación, salvaguardia o promoción del patrimonio cultural.	10
El distrito o municipio **NO** cuenta con iniciativas o empresas cuyas actividades se encuentren asociadas a la preservación, salvaguardia o promoción del patrimonio cultural.	0

Fuente de consulta: *documentación oficial de la alcaldía distrital o municipal.*
Anexo plantilla: *lista de iniciativas públicas y privadas o empresas (nombre, actividad o patrimonio que salvaguarda, número de personas vinculadas y tiempo en la actividad) cuyas actividades se encuentran asociadas a la preservación, salvaguardia o promoción del patrimonio cultural del distrito o municipio.*

19. **Bienes de Interés Cultural:** se consideran Bienes de Interés Cultural (BIC) aquellos bienes materiales que las autoridades competentes han declarado, como monumentos, áreas de conservación histórica, arqueológica o arquitectónica, conjuntos históricos, o mediante otras denominaciones vigentes antes de la promulgación de la ley 1185 de 2008. Los BIC, pueden ser de los ámbitos nacional, departamental, distrital, municipal, de los territorios indígenas o de las comunidades negras de que trata la Ley 70 de 1993 (Ministerio de Cultura, 2020).

Evaluación

CRITERIO	PUNTAJE
Resultado desde **40,1% o más** atractivos turísticos culturales (clasificados como patrimonio cultural material inmueble) declarados Bienes de Interés Cultural sobre el número de atractivos turísticos culturales del distrito o municipio.	10
Resultado entre el **30,1% y el 40%** de atractivos turísticos culturales (clasificados como patrimonio cultural material inmueble) declarados Bienes de Interés Cultural sobre el número de atractivos turísticos culturales del distrito o municipio.	8
Resultado entre el **20,1% y el 30%** de atractivos turísticos culturales (clasificados como patrimonio cultural material inmueble) declarados Bienes de Interés Cultural sobre el número de atractivos turísticos culturales del distrito o municipio.	6
Resultado entre el **10,1% y el 20%** de atractivos turísticos culturales (clasificados como patrimonio cultural material inmueble) declarados Bienes de Interés Cultural sobre el número de atractivos turísticos culturales del distrito o municipio.	4
Resultado mayor que **0% y hasta el 10%** de atractivos turísticos culturales (clasificados como patrimonio cultural material inmueble) declarados Bienes de Interés Cultural sobre el número de atractivos turísticos culturales del distrito o municipio.	2
El distrito o municipio **NO** cuenta con Bienes de Interés Cultural.	0

1. Para este indicador usar la siguiente fórmula: (número de atractivos turísticos culturales clasificados como patrimonio cultural material inmueble del distrito o municipio declarados Bienes de Interés Cultural / número de atractivos turísticos culturales clasificados como patrimonio cultural material inmueble del distrito o municipio) x 100.

Fuente de consulta: *Ministerio de Cultura, lista de bienes declarados Bien de Interés Cultural del ámbito nacional y Viceministerio de Turismo, documento consolidado de inventarios turísticos.*

20. **Participación del turismo en el PIB departamental:** participación de la actividad turística en el Producto Interno Bruto departamental (total de bienes y servicios producidos por un departamento durante un periodo determinado).

Evaluación

CRITERIO	PUNTAJE
El porcentaje de contribución de las actividades turísticas al PIB departamental es superior a **27,12%**	10
El porcentaje de contribución de las actividades turísticas al PIB departamental esta entre **20,34% y 27,11%**	8
El porcentaje de contribución de las actividades turísticas al PIB departamental esta entre **13,56% y 20,33%**	6
El porcentaje de contribución de las actividades turísticas al PIB departamental esta entre **6,78% y 13,55%**	4
El porcentaje de contribución de las actividades turísticas al PIB departamental es mayor que **0% y hasta 6,77%**	2
El porcentaje de contribución de las actividades turísticas al PIB departamental es **0%.**	0

1. Ver indicador "Participación del turismo en el PIB".

Fuente de consulta: *Índice de Competitividad Turística Regional de Colombia (departamentos) del año anterior al que se implemente la metodología. Indicador "Participación del turismo en el PIB".*

21. **Programas o actividades de conservación y protección ambiental en el contexto de viajes y turismo:** fomento del cuidado, conservación y protección de los destinos, mediante acciones pedagógicas de carácter ambiental, que permitan sensibilizar a las comunidades, prestadores de servicios y turistas acerca de la responsabilidad y compromiso en el uso sostenible de los recursos para el desarrollo de actividades turísticas.

Evaluación

CRITERIO	PUNTAJE
Cuenta con un programa de conservación y protección ambiental dirigido al sector turístico.	10
Realizó o participó en actividades para la conservación y protección ambiental dirigidas al sector turístico.	5
No ha desarrollado ningún programa o acciones de conservación en el último año para el sector turístico.	0

Fuente de consulta: *documentación oficial de la alcaldía municipal o distrital.*
Anexo plantilla: *el distrito o municipio adjuntará la plantilla con la información asociada al fomento del cuidado, conservación y protección ambiental del distrito o municipio.*
En caso de que la respuesta sea positiva, el municipio adjuntará el soporte de programas o actividades de conservación y cuidado ambiental en el último año.

22. **Empresas certificadas en Normas Técnicas Sectoriales de Sostenibilidad:** prestadores de servicios turísticos que cuentan con una certificación vigente en la Norma Técnica Sectorial que le corresponda, otorgado por un organismo evaluador de la conformidad, avalado por el Organismo Nacional de Acreditación de Colombia – ONAC.

Evaluación

CRITERIO	PUNTAJE
El porcentaje de prestadores de servicios turísticos certificados en Normas Técnicas Sectoriales de sostenibilidad es igual o mayor a **80,1%** sobre el total de prestadores de servicios turísticos con RNT activo del distrito o municipio*	10
El porcentaje de prestadores de servicios turísticos certificados en Normas Técnicas Sectoriales de sostenibilidad está entre **60,1% y 80%** sobre el total de prestadores de servicios turísticos con RNT activo del distrito o municipio*	8
El porcentaje de prestadores de servicios turísticos certificados en Normas Técnicas Sectoriales de sostenibilidad está entre **40,1% y 60%** sobre el total de prestadores de servicios turísticos con RNT activo del distrito o municipio*	6
El porcentaje de prestadores de servicios turísticos certificados en Normas Técnicas Sectoriales de sostenibilidad está entre **20,1% y 40%** sobre el total de prestadores de servicios turísticos con RNT activo del distrito o municipio*	4
El porcentaje de prestadores de servicios turísticos certificados en Normas Técnicas Sectoriales de sostenibilidad es mayor que **0% y hasta 20%** sobre el total de prestadores de servicios turísticos con RNT activo del distrito o municipio*	2
El distrito o municipio **NO** cuenta con prestadores de servicios turísticos certificados en Normas Técnicas Sectoriales de sostenibilidad.	0

1. *Para este indicador usar la siguiente fórmula: (número de prestadores de servicios turísticos certificados en Normas Técnicas Sectoriales de Sostenibilidad / número de prestadores de servicios turísticos con la posibilidad de certificarse en las Normas Técnicas Sectoriales de sostenibilidad) x 100.*

Fuente de consulta: *Viceministerio de Turismo, base de empresas certificadas en Normas Técnicas Sectoriales de Sostenibilidad y base de Registro Nacional de Turismo actualizada.*

23. Destinos certificados en Normas Técnicas Sectoriales de Sostenibilidad: destinos que cuentan con una certificación vigente en las Normas Técnicas Sectoriales para destinos (NTS TS 001 – 1 y NTS TS 001 – 2), otorgado por un organismo evaluador de la conformidad avalado por el Organismo Nacional de Acreditación de Colombia – ONAC.

Evaluación

CRITERIO	PUNTAJE
El distrito o municipio cuenta con **1 o más** certificaciones en las Normas Técnicas Sectoriales de sostenibilidad de destinos.	10
El distrito o municipio se encuentra **en proceso** de implementación de una Norma Técnica Sectorial de sostenibilidad*.	5
El distrito o municipio **NO** cuenta con certificaciones en las Normas Técnicas Sectoriales de sostenibilidad de destinos.	0

**El municipio tendrá que contar con la documentación que soporte el proceso de implementación para obtener este puntaje.*

Fuente de consulta: *Viceministerio de Turismo, base de destinos o áreas certificadas en Normas Técnicas Sectoriales de Sostenibilidad.*
Anexo: *en caso de que el puntaje sea 5, adjuntar la documentación de soporte del proceso de implementación. Si el puntaje es 10, adjuntar el documento de certificación del destino.*

EVALUACIÓN DEL EJE
ASPECTOS ASOCIADOS A LA SOSTENIBILIDAD TURÍSTICA (20%)

Como resultado de la evaluación de los indicadores previamente descritos, se generará un puntaje para el eje "Aspectos asociados a la sostenibilidad turística" que será calculado realizando la división de la sumatoria del total de los criterios ya evaluados en el eje en el número total de criterios, que para este caso es **13**. El resultado será multiplicado por **20%** que corresponde al peso porcentual del eje sobre el componente de oferta.

EJE 3
INFRAESTRUCTURA Y CONDICIONES BÁSICAS DEL DESTINO

El desarrollo de actividades turísticas implica intervenciones físicas que además de garantizar la calidad y seguridad de la experiencia del visitante, deben asegurar el bienestar y la calidad de vida de las comunidades de destino.

Este eje permite evaluar indicadores asociados a la seguridad, el estado actual de los servicios básicos necesarios para la prestación de servicios turísticos y las condiciones presentes de las infraestructuras turísticas en el distrito o municipio en evaluación. Una calificación superior en los indicadores incluidos en este eje, permitirá avanzar en dirección hacia el desarrollo sostenible y seguro de los territorios.

24. **Control y sanciones en la prestación de servicios turísticos:** hace referencia a las denuncias y demandas presentadas por los turistas (cliente) por incumplimiento en la prestación del servicio o las demás normas que regulan la actividad turística (SIC, 2020). *Ver artículo 143 del Decreto 2106 de 2019.*

Evaluación

CRITERIO	PUNTAJE
El total de prestadores de servicios turísticos del distrito o municipio **NO** cuenta con denuncias y demandas presentadas ante la SIC durante el último año.	10
Las denuncias y demandas presentadas ante la SIC equivalen a un porcentaje mayor que **0% y hasta el 20%** sobre el total de empresarios con Registro Nacional de Turismo en el distrito o municipio*	8
Las denuncias y demandas presentadas ante la SIC equivalen a un porcentaje entre **21% y 40%** sobre el total de empresarios con Registro Nacional de Turismo en el distrito o municipio*	6
Las denuncias y demandas presentadas ante la SIC equivalen a un porcentaje entre **41% y 60%** sobre el total de empresarios con Registro Nacional de Turismo en el distrito o municipio*	4
Las denuncias y demandas presentadas ante la SIC equivalen a un porcentaje entre **61% y 80%** sobre el total de empresarios con Registro Nacional de Turismo en el distrito o municipio*	2
Las denuncias y demandas presentadas ante la SIC equivalen a un porcentaje entre **81% y 100%** sobre el total de empresarios con Registro Nacional de Turismo en el distrito o municipio*	0

**El municipio tendrá en cuenta la cantidad de denuncias y demandas presentadas en el año anterior a la implementación del instrumento. Para calcular el porcentaje de denuncias y demandas presentadas por los turistas usar la siguiente fórmula de cálculo: número de prestadores de servicios turísticos con denuncias y demandas ante la SIC / total de prestadores de servicios turísticos con Registro Nacional de Turismo activo en el distrito o municipio.*

Fuente de consulta: *base de denuncias y demandas por municipio de la Superintendencia de Industria y Comercio (SIC).*

25. **Número de accidentes que afectan a turistas:** actos o sucesos imprevistos que causan daños o afectaciones a turistas (nacionales y extranjeros) en atractivos o espacios turísticos.

Evaluación*

CRITERIO	PUNTAJE
En el distrito o municipio **NO** se han presentado accidentes que afectan a turistas durante el último año (enero a diciembre).	10
En el distrito o municipio **SÍ** se han presentado accidentes que afectan a turistas durante el último año (enero a diciembre).	0

**En futuras mediciones será necesario contar con información cuantitativa específica de este indicador. Se sugiere consultar esta información con las secretarías de salud distritales o municipales.*

***Fuente de consulta**: documentación oficial del distrito o municipio.*

26. **Actos de terrorismo:** acciones cuyo objetivo sea "provocar o mantener en estado de zozobra o terror a la población o a un sector de ella, mediante actos que pongan en peligro la vida, la integridad física o la libertad de las personas o las edificaciones o medios de comunicación, transporte, procesamiento o conducción de fluidos o fuerzas motrices, valiéndose de medios capaces de causar estragos" (Ley 599 de 2000).

Evaluación

CRITERIO	PUNTAJE
El municipio **Y** todos los municipios con los que limita, **NO** se han visto afectados por actos de terrorismo en el último año*	10
El municipio **O** alguno de los municipios con los que limita, se han visto afectados por **1 o más** actos de terrorismo en el último año*	5
El municipio **Y** los municipios con los que limita, se han visto afectados por **1 o más** actos de terrorismo en el último año*	0

**El municipio tendrá en cuenta los actos terroristas del año anterior a la implementación de la metodología y que registre el reporte del Ministerio de Defensa.*

Fuente de consulta: *Ministerio de Defensa de Colombia, Viceministerio para las Políticas y Asuntos Internacionales. Dirección de Estudios Estratégicos - Grupo de Información Estadística o documentación oficial del distrito o municipio.*

27. Homicidios: "toda muerte causada por cualquier tipo de arma a excepción de aquellos que fueren cometidos en accidentes de tránsito" (Ley 599 de 2000).

Evaluación

CRITERIO	PUNTAJE
El distrito o municipio **NO** registró homicidios en el último año*.	10
El distrito o municipio registra entre **1 y 22** homicidios por cada 100.000 habitantes en el último año*.	9
El distrito o municipio registra entre **23 y 44** homicidios por cada 100.000 habitantes en el último año*.	8
El distrito o municipio registra entre **45 y 66** homicidios por cada 100.000 habitantes en el último año*.	7
El distrito o municipio registra entre **67 y 85** homicidios por cada 100.000 habitantes en el último año*.	6
El distrito o municipio registra entre **86 y 104** homicidios por cada 100.000 habitantes en el último año*.	5
El distrito o municipio registra entre **105 y 123** homicidios por cada 100.000 habitantes en el último año*.	4
El distrito o municipio registra entre **124 y 142** homicidios por cada 100.000 habitantes en el último año*.	3
El distrito o municipio registra entre **143 y 161** homicidios por cada 100.000 habitantes en el último año*.	2
El distrito o municipio registra entre **162 y 180** homicidios por cada 100.000 habitantes en el último año*.	1
El distrito o municipio registró **181 o más** homicidios por cada 100.000 habitantes en el último año*.	0

1. El distrito o municipio tendrá en cuenta los homicidios del año anterior a la implementación de la metodología y que registre el Instituto Nacional de Medicina Legal y Ciencias Forenses.

Fuente de consulta: *Instituto Nacional de Medicina Legal y Ciencias Forenses o documentación oficial del distrito o municipio.*

28. **Policía de Turismo:** las unidades de Policía de Turismo pertenecen a la Dirección de Protección y Servicios Especiales de la Policía Nacional. Son responsables de adelantar labores de vigilancia y control de los atractivos turísticos, atender labores de información turística, orientar a los turistas y canalizar las quejas presentadas, apoyar investigaciones adelantadas por el Viceministerio de Turismo y otras que les sean asignadas (Ley 300 de 1996).

Evaluación

CRITERIO	PUNTAJE
El distrito o municipio **SÍ** cuenta con Policía de Turismo.	10
El distrito o municipio **NO** cuenta con Policía de Turismo.	0

Fuente de consulta: *Policía Nacional. Número de Policías de Turismo por municipio.*

29. **Accidentalidad vial en temporadas turísticas:** "eventos generalmente involuntarios, generados al menos por un vehículo en movimiento, que causa daños a personas y bienes involucrados en él y que igualmente afecta la normal circulación de los vehículos que se movilizan por la vía o las vías comprendidas en el lugar o dentro de la zona de influencia del hecho" (Ley 769 del 2002) en temporadas turísticas (15 de diciembre al 15 de enero, Semana Santa, 15 de junio al 15 de julio, semana de receso de octubre, puentes festivos y eventos atípicos y ocasiones especiales del distrito o municipio que generen movilización de turistas fuera de las temporadas previamente mencionadas).

Evaluación

CRITERIO	PUNTAJE
El distrito o municipio cuenta con un registro de accidentalidad vial en temporadas turísticas y **NO** presenta accidentes*.	10
El distrito o municipio cuenta con un registro de accidentalidad vial en temporadas turísticas, **SÍ** presenta accidentes* **Y** cuenta con una estrategia articulada con otras carteras para mitigar la accidentalidad vial en temporadas turísticas.	8
El distrito o municipio cuenta con un registro de accidentalidad vial en temporadas turísticas, **SÍ** presenta accidentes* **Y** adelanta acciones para mitigar la accidentalidad vial en temporadas turísticas, de forma ocasional.	6
El distrito o municipio **NO** cuenta con un registro de accidentalidad vial en temporadas turísticas y **NO** presenta accidentes*.	4
El distrito o municipio cuenta con un registro de accidentalidad vial en temporadas turísticas, **SÍ** presenta accidentes* y **NO** adelanta acciones para mitigar la accidentalidad vial en temporadas turísticas.	2
El distrito o municipio **NO** cuenta con un registro de accidentalidad vial en temporadas turísticas y **SÍ** presenta accidentes*.	0

**El reporte de accidentalidad vial corresponderá únicamente a los accidentes de la vigencia anual anterior (enero a diciembre).*

Fuente de consulta: *documentación oficial de la alcaldía distrital o municipal.*
Anexo plantilla: *documento que incluya información asociada a los accidentes viales que se presentan en el distrito o municipio.*

30. **Comités Departamentales de Seguridad Turística:** tienen como objetivo promover y coordinar medidas de prevención y control y ser el enlace de las fuerzas de seguridad civil y militar, las autoridades departamentales de turismo, los empresarios y otros actores que se consideren necesarios para diseñar medidas y estrategias y generar compromisos para la seguridad del turista. Reglamentados por el Decreto 945 de mayo de 2014, según las disposiciones de la Ley 1558 de 2012.

Evaluación

CRITERIO	PUNTAJE
El distrito o municipio participa de forma activa y permanente en la preparación y desarrollo de los Comités Departamentales de Seguridad Turística.	10
El distrito o municipio participa de forma esporádica en la preparación y desarrollo de los Comités Departamentales de Seguridad Turística.	5
El distrito o municipio **NO** participa con regularidad en la preparación y el desarrollo de los Comités Departamentales de Seguridad Turística.	0

Fuente de consulta: *documentación oficial del distrito o municipio.*
Anexo plantilla: *diligencie la plantilla incluyendo la información asociada a la participación del distrito o municipio en el desarrollo de los Comités Departamentales de Seguridad Turística.*

31. **Delitos cometidos hacia turistas:** crímenes asociados a homicidios, homicidios en accidentes de tránsito, lesiones personales, hurto, delitos sexuales, amenazas u otros que puedan afectar la experiencia de los turistas en el distrito o municipio.

Evaluación

CRITERIO	PUNTAJE
El distrito o municipio **NO** cuenta con denuncias oficiales realizadas por turistas nacionales o extranjeros.	10
Los delitos cometidos hacia turistas equivalen a un porcentaje mayor que **0% y hasta el 20%** sobre el total de delitos reportados en el distrito o municipio.	8
Los delitos cometidos hacia turistas equivalen a un porcentaje entre el **20,1% y 40%** sobre el total de delitos reportados en el distrito o municipio.	6
Los delitos cometidos hacia turistas equivalen a un porcentaje entre el **40,1% y 60%** sobre el total de delitos reportados en el distrito o municipio.	4
Los delitos cometidos hacia turistas equivalen a un porcentaje entre el **60,1% y 80%** sobre el total de delitos reportados en el distrito o municipio.	2
Los delitos cometidos hacia turistas equivalen a un porcentaje entre el **80,1% y 100%** sobre el total de delitos reportados en el distrito o municipio.	0

1. Para este indicador emplear la siguiente fórmula: (número de delitos cometidos hacia turistas / número total de delitos cometidos en el distrito o municipio) x 100.

Fuente de consulta: *Policía Nacional*. Sistema de Información Estadístico, Delincuencial, Contravencional y Operativo - SIEDCO. Turistas víctimas de delitos por municipio en 2019. Documentación oficial del distrito o municipio (número total de delitos cometidos en el distrito o municipio)

32. Prestadoras de servicios de salud: "entidades oficiales, mixtas, privadas, comunitarias y solidarias, organizadas para la prestación de los servicios de salud a los afiliados del Sistema General de Seguridad Social en Salud, dentro de las Entidades Promotoras de Salud o fuera de ellas. Son entidades organizadas para la prestación de los servicios de salud, que tienen como principios básicos la calidad y la eficiencia, cuentan con autonomía administrativa, técnica y financiera, y deben propender por la libre concurrencia de sus acciones" (Corte Constitucional de Colombia, 2008).

Evaluación

CRITERIO	PUNTAJE
El número de prestadores de servicios de salud públicos y privados en el distrito o municipio equivalen a un porcentaje igual o mayor a **1.61%** sobre el total de la población del distrito o municipio.	10
El número de prestadores de servicios de salud públicos y privados en el distrito o municipio equivalen a un porcentaje entre **1.21% y 1.60%** sobre el total de la población del distrito o municipio.	8
El número de prestadores de servicios de salud públicos y privados en el distrito o municipio equivalen a un porcentaje entre **0,81% y 1.20%** sobre el total de la población del distrito o municipio.	6
El número de prestadores de servicios de salud públicos y privados en el distrito o municipio equivalen a un porcentaje entre **0,41% y 0.80%** sobre el total de la población del distrito o municipio.	4
El número de prestadores de servicios de salud públicos y privados en el distrito o municipio equivalen a un porcentaje mayor que **0% y hasta 0.40%** sobre el total de la población del distrito o municipio.	2
El distrito o municipio **NO** cuenta con prestadores de servicios de salud públicos o privados.	0

1. Ingrese al portal del "Directorio de Prestadores - Información de Prestadores de Servicios de Salud" y en la pestaña "Directorio de prestadores" seleccione su departamento y distrito o municipio haga clic en buscar (no es necesario seleccionar otros filtros). El sistema mostrará el número de registros encontrado para su distrito o municipio.

2. Para este indicador emplear la siguiente fórmula de cálculo: (número de Prestadores de Servicios de Salud registradas en el REPS para el distrito o municipio/número de habitantes del distrito o municipio) x 1.000.

Fuente de consulta: Ministerio de Salud, https://prestadores.minsalud.gov.co/habilitacion/. Registro Especial de Prestadores de Servicios de Salud – REPS (ingresar con usuario y contraseña predeterminados), ver Directorio de Prestadores - Información de Prestadores de Servicios de Salud. Número de habitantes del distrito o municipio.

33. **Infraestructura aeronáutica nacional:** "todo aeródromo especialmente equipado y usado regularmente para pasajeros y carga y que a juicio de la UAEAC (Unidad Administrativa Especial de Aeronáutica Civil), posee instalaciones y servicios de infraestructura aeronáutica suficientes para ser operados en la aviación civil. Se considera de servicio nacional, cuando su operación es exclusiva entre puntos de origen y destino situados dentro del territorio nacional" (Resolución 01092 de 2007).

Evaluación

CRITERIO	PUNTAJE
Cuenta con un espacio físico que sirve como terminal, y **SI** tiene servicio de baños, compras, oficinas para la comercialización de tiquetes, enfermería, cajeros electrónicos, área de comidas, Punto de Información Turística o informador turístico, asignación de taxis seguros, servicios de seguridad, WiFi gratuito, parqueaderos, personal 24 horas, servicios para personas con discapacidad, duchas, página web, casilleros y servicios de vacunación.	10
Cuenta con un espacio físico que sirve como terminal, y **SI** tiene servicio de baños, compras, oficinas para la comercialización de tiquetes, enfermería, cajeros electrónicos, área de comidas, Punto de Información Turística o informador turístico, asignación de taxis seguros, servicios de seguridad y WiFi gratuito.	8
Cuenta con un espacio físico que sirve como terminal, y **SI** tiene servicio de baños, compras, oficinas para la comercialización de tiquetes, enfermería y cajeros electrónicos.	6
Cuenta con un aeródromo*, pero **NO** tiene servicio de baños, compras, oficinas para la comercialización de tiquetes, enfermería o cajeros electrónicos.	4
El distrito o municipio **NO** identifica ningún aeropuerto como principal receptor de visitantes que se dirijan hacia su destino.	2

1. Evaluación del criterio a nivel departamental.

2. Hace referencia al aeropuerto nacional seleccionado como principal receptor de visitantes que se dirigen al distrito o municipio.

** Aeródromo: área definida de tierra o de agua (que incluye todas sus edificaciones, instalaciones y equipos) destinado total o parcialmente a la llegada, salida y movimiento en superficie de aeronaves (Resolución 01624 de 2007).*

Fuente de consulta: *información propia del departamento, distrito o municipio.*
Agencia Nacional de Infraestructura (ANI).
Unidad Administrativa Especial de Aeronáutica Civil (UAEAC).
Cuadro de información: *indique el nombre del aeropuerto seleccionado como principal receptor de visitantes que se dirigen al distrito o municipio (entiéndase como "principal" el aeropuerto más utilizado por los turistas para llegar al distrito o municipio, aunque deban utilizar otros medios de transporte para llegar al destino).*

34. Infraestructura aeronáutica internacional: "aquel que es designado por la UAEAC (Unidad Administrativa Especial de Aeronáutica Civil), como de entrada o salida para el tráfico aéreo internacional y en él se llevarán a cabo los trámites de aduana, inmigración o emigración, sanidad pública, reglamentación veterinaria y fitosanitaria y procedimientos similares.

Además de las instalaciones y servicios necesarios para los controles de aduana, migración y sanitarios, de que trata el párrafo anterior; todo aeropuerto internacional, deberá contar, con servicios de tránsito aéreo, telecomunicaciones aeronáuticas, información aeronáutica, meteorología aeronáutica, ayudas a la navegación, salvamento y extinción de incendios, búsqueda y salvamento, despacho y servicios de escala, pista con número de clave de 3 o 4, calles de rodaje, plataforma para parqueo de aeronaves, iluminación y señalización, talleres de mantenimiento aeronáutico, aprovisionamiento de combustible de aviación, terminales para pasajeros, equipajes y carga, así como facilidades de transporte terrestre y conectividad con los centros urbanos, todo ello durante el tiempo en que esté operando y contar con el personal calificado necesario para atender todos y cada uno de dichos servicios" (Resolución 01092 de 2007).

Evaluación

CRITERIO	PUNTAJE
El departamento al que pertenece el distrito o municipio cuenta con un aeropuerto internacional que cumple **EN SU TOTALIDAD** con las características señaladas en la definición de este indicador.	10
El departamento al que pertenece el distrito o municipio cuenta con un aeropuerto internacional que cumple **PARCIALMENTE** con las características señaladas en la definición de este indicador.	7
El departamento al que pertenece el distrito o municipio **NO** cuenta con un aeropuerto internacional.	5

1. Evaluación del criterio a nivel departamental.

Fuente de consulta: *Información propia del departamento, distrito o municipio.*
Agencia Nacional de Infraestructura (ANI).
Unidad Administrativa Especial de Aeronáutica Civil (UAEAC).
Cuadro de información: *indique el nombre del aeropuerto internacional evaluado.*

35. **Terminales de transporte terrestre:** unidad de servicios permanentes, junto a los equipos, órganos de administración, servicios a los usuarios, a las empresas de transporte y a su parque automotor, donde se concentran las empresas autorizadas o habilitadas que cubren rutas que tienen como origen, destino o tránsito el respectivo municipio o localidad (Ministerio de Transporte (Decreto 2762 de 2001).

Evaluación

CRITERIO	PUNTAJE
Cuenta con un espacio físico que sirve como terminal, y **SI** tiene servicio de baños, compras, oficinas para la comercialización de tiquetes, enfermería, cajeros electrónicos, área de comidas, Punto de Información Turística o informador turístico, asignación de taxis seguros, servicios de seguridad, WiFi gratuito, parqueaderos, personal 24 horas, servicios para personas con discapacidad, duchas, página web, casilleros y servicios de vacunación.	10
Cuenta con un espacio físico que sirve como terminal, y **SI** tiene servicio de baños, compras, oficinas para la comercialización de tiquetes, enfermería, cajeros electrónicos, área de comidas, Punto de Información Turística o informador turístico, asignación de taxis seguros, servicios de seguridad y WiFi gratuito.	8
Cuenta con un espacio físico que sirve como terminal, y **SI** tiene servicio de baños, compras, oficinas para la comercialización de tiquetes, enfermería y cajeros electrónicos.	6
Cuenta con un espacio físico que sirve como terminal, pero **NO** tiene servicio de baños, compras, oficinas para la comercialización de tiquetes, enfermería o cajeros electrónicos.	4
El municipio **NO** cuenta con un terminal de transporte terrestre.	2

Fuente de consulta: *Información propia del distrito o municipio. Ministerio de Transporte.*

36. Índice de penetración del servicio de internet banda ancha: "mide el número de suscriptores con acceso fijo a internet para cada distrito o municipio" (Ministerio de las Tecnologías de la Información y las Comunicaciones, 2020).

Evaluación

CRITERIO	PUNTAJE
El distrito o municipio cuenta con un índice de penetración de accesos fijos a internet mayor a **26,43%**	10
El distrito o municipio cuenta con un índice de penetración de accesos fijos a internet entre **23,50%** y **26,42%**	9
El distrito o municipio cuenta con un índice de penetración de accesos fijos a internet entre **20,56%** y **23,49%**	8
El distrito o municipio cuenta con un índice de penetración de accesos fijos a internet entre **17,62%** y **20,55%**	7
El distrito o municipio cuenta con un índice de penetración de accesos fijos a internet entre **14,69%** y **17,61%**	6
El distrito o municipio cuenta con un índice de penetración de accesos fijos a internet entre **11,75%** y **14,68%**	5
El distrito o municipio cuenta con un índice de penetración de accesos fijos a internet entre **8,81%** y **11,74%**	4
El distrito o municipio cuenta con un índice de penetración de accesos fijos a internet entre **5,87%** y **8,80%**	3
El distrito o municipio cuenta con un índice de penetración de accesos fijos a internet entre **2,94%** y **5,86%**	2
El distrito o municipio cuenta con un índice de penetración de accesos fijos a internet mayor a **0%** y hasta **2,93%**	1

*1. El distrito o municipio tendrá en cuenta los datos del boletín trimestral **más reciente.***

2. Consultar en el portal web https://colombiatic.mintic.gov.co/ el documento Excel del "Informe Trimestral de las TIC" más reciente, pestaña "Accesos fijos a internet por departamento, municipio y población", dato de la columna del trimestre más reciente.

Fuente de consulta: *Boletín Trimestral de las TIC (más reciente), Ministerio de las Tecnologías de la Información y las Comunicaciones: https://colombiatic.mintic.gov.co/*

37. Velocidad de conexión de internet banda ancha: "capacidad de transmisión cuyo ancho de banda es suficiente para permitir, de manera combinada, la provisión de voz, datos y video, ya sea de manera alámbrica o inalámbrica" (Resolución 3067 de 2011).

Evaluación

CRITERIO	PUNTAJE
El departamento al que pertenece el distrito o municipio cuenta con un puntaje **mayor que 8,01** en el criterio "velocidad de conexión a internet por banda ancha".	10
El departamento al que pertenece el distrito o municipio cuenta con un puntaje **entre 6,01 y 8** en el criterio "velocidad de conexión a internet por banda ancha".	8
El departamento al que pertenece el distrito o municipio cuenta con un puntaje **entre 4,01 y 6** en el criterio "velocidad de conexión a internet por banda ancha".	6
El departamento al que pertenece el distrito o municipio cuenta con un puntaje **entre 2,01 y 4** en el criterio "velocidad de conexión a internet por banda ancha".	4
El departamento al que pertenece el distrito o municipio cuenta con un puntaje **entre 0,01 y 2** en el criterio "velocidad de conexión a internet por banda ancha".	2
El departamento al que pertenece el distrito o municipio cuenta con un puntaje **igual a 0** en el criterio "velocidad de conexión a internet por banda ancha".	0

1. Ver indicador "Velocidad de conexión a internet por banda ancha" en el Índice de Competitividad Turística Regional de Colombia, Centro de Pensamiento Turístico Colombia (departamentos).
2. Evaluación del criterio a nivel departamental.

Fuente de consulta: *Índice de Competitividad Turística Regional de Colombia, Centro de Pensamiento Turístico Colombia (departamentos) del año inmediatamente anterior al que se implemente la metodología.*

38. Llamadas caídas en la red de telefonía móvil: hace referencia a las llamadas realizadas a través de teléfonos móviles que sufren interrupciones en su desarrollo, afectando el buen servicio de comunicación.

CRITERIO	PUNTAJE
El departamento al que pertenece el distrito o municipio cuenta con un puntaje **mayor que 8,01** en el criterio "llamadas caídas en la red de telefonía móvil".	10
El departamento al que pertenece el distrito o municipio cuenta con un puntaje **entre 6,01 y 8** en el criterio "llamadas caídas en la red de telefonía móvil".	8
El departamento al que pertenece el distrito o municipio cuenta con un puntaje **entre 4,01 y 6** en el criterio "llamadas caídas en la red de telefonía móvil".	6
El departamento al que pertenece el distrito o municipio cuenta con un puntaje **entre 2,01 y 4** en el criterio "llamadas caídas en la red de telefonía móvil".	4
El departamento al que pertenece el distrito o municipio cuenta con un puntaje **entre 0,01 y 2** en el criterio "llamadas caídas en la red de telefonía móvil".	2
El departamento al que pertenece el distrito o municipio cuenta con un puntaje **igual a 0** en el criterio "llamadas caídas en la red de telefonía móvil".	0

1. Ver indicador "Llamadas caídas en la red de telefonía móvil" en el Índice de Competitividad Turística Regional de Colombia, Centro de Pensamiento Turístico Colombia (departamentos).
2. Evaluación del criterio a nivel departamental.

Fuente de consulta: *Índice de Competitividad Turística Regional de Colombia, Centro de Pensamiento Turístico Colombia (departamentos) del año inmediatamente anterior al que se implemente la metodología.*

39. **Cobertura del servicio de acueducto:** porcentaje de predios con acceso al servicio de acueducto en el área urbana y rural del distrito o municipio (Superintendencia de Servicios Públicos, 2020).

Evaluación

CRITERIO	PUNTAJE
El municipio cuenta con un porcentaje de cobertura del servicio de acueducto entre **80,1%** y **100%**	10
El municipio cuenta con un porcentaje de cobertura de servicios de acueducto entre **70,1% y 80%**	8
El municipio cuenta con un porcentaje de cobertura de servicios de acueducto entre **50,1% y 70%.**	6
El municipio cuenta con un porcentaje de cobertura de servicios de acueducto entre que **30,1% y 50%.**	4
El municipio cuenta con un porcentaje de cobertura de servicios de acueducto mayor que **0% y hasta 30%**	2
El municipio **NO** cuenta servicio de acueducto.	0

Fuente de consulta: *información oficial del distrito o municipio reportada a la Superintendencia de Servicios Públicos, Sistema Único de Información de Servicios Públicos Domiciliarios SUI, módulo "alcaldes", "reporte de estratificación y coberturas".*
Cuadro de información: *escriba el porcentaje de cobertura del servicio de acueducto, registrado por última vez en el Sistema Único de Información de Servicios Públicos Domiciliarios – SUI de la Superintendencia de Servicios Públicos.*

40. **Cobertura del servicio de alcantarillado:** porcentaje de predios con acceso al servicio de alcantarillado en el área urbana y rural del distrito o municipio (Superintendencia de Servicios Públicos, 2020).

Evaluación

CRITERIO	PUNTAJE
El municipio cuenta con un porcentaje de cobertura del servicio de alcantarillado entre el **80,1%** y **100%**	10
El municipio cuenta con un porcentaje de cobertura de servicios de alcantarillado entre **70,1% y 80%**	8
El municipio cuenta con un porcentaje de cobertura de servicios de alcantarillado entre **50,1% y 70%.**	6
El municipio cuenta con un porcentaje de cobertura de servicios de alcantarillado entre **30,1% y 50%.**	4
El municipio cuenta con un porcentaje de cobertura de servicios de alcantarillado mayor **0% y hasta 30%**	2
El municipio **NO** cuenta servicio de alcantarillado.	0

Fuente de consulta: *información oficial del distrito o municipio reportada a la Superintendencia de Servicios Públicos, Sistema Único de Información de Servicios Públicos Domiciliarios SUI, módulo "alcaldes", "reporte de estratificación y coberturas".*
Cuadro de información: *escriba el porcentaje de cobertura del servicio de alcantarillado, registrado por última vez en el Sistema Único de Información de Servicios Públicos Domiciliarios – SUI de la Superintendencia de Servicios Públicos.*

41. **Cobertura del servicio de aseo:** porcentaje de predios con acceso al servicio de aseo en el área urbana y rural del distrito o municipio (Superintendencia de Servicios Públicos, 2020).

Evaluación

CRITERIO	PUNTAJE
El municipio cuenta con un porcentaje de cobertura del servicio de aseo entre **80,1%** y **100%**	10
El municipio cuenta con un porcentaje de cobertura de servicios de aseo entre **70,1% y 80%**	8
El municipio cuenta con un porcentaje de cobertura de servicios de aseo entre **50,1% y 70%.**	6
El municipio cuenta con un porcentaje de cobertura de servicios de aseo entre que **30,1% y 50%.**	4
El municipio cuenta con un porcentaje de cobertura de servicios de aseo mayor que **0% y hasta 30%**	2
El municipio **NO** cuenta servicio de aseo.	0

Fuente de consulta: *información oficial del distrito o municipio reportada a la Superintendencia de Servicios Públicos, Sistema Único de Información de Servicios Públicos Domiciliarios SUI, módulo "alcaldes", "reporte de estratificación y coberturas".*
Cuadro de información: *escriba el porcentaje de cobertura del servicio de aseo, registrado por última vez en el Sistema Único de Información de Servicios Públicos Domiciliarios – SUI de la Superintendencia de Servicios Públicos.*

42. **Cobertura del servicio de energía eléctrica:** porcentaje de predios con acceso al servicio de aseo en el área urbana y rural del distrito o municipio (Superintendencia de Servicios Públicos, 2020).

Evaluación

CRITERIO	PUNTAJE
El municipio cuenta con un porcentaje de cobertura del servicio de energía eléctrica entre el **80,1%**	10
El municipio cuenta con un porcentaje de cobertura de servicios de energía eléctrica entre **70,1% y 80%**	8
El municipio cuenta con un porcentaje de cobertura de servicios de energía eléctrica entre **50,1% y 70%.**	6
El municipio cuenta con un porcentaje de cobertura de servicios de energía eléctrica entre que **30,1% y 50%.**	4
El municipio cuenta con un porcentaje de cobertura de servicios de energía eléctrica mayor que **0% y hasta 30%**	2
El municipio **NO** cuenta servicio de energía eléctrica.	0

Fuente de consulta: *información oficial del distrito o municipio reportada a la Superintendencia de Servicios Públicos, Sistema Único de Información de Servicios Públicos Domiciliarios SUI, módulo "alcaldes", "reporte de estratificación y coberturas".*
Cuadro de información: *escriba el porcentaje de cobertura del servicio de energía eléctrica, registrado por última vez en el Sistema Único de Información de Servicios Públicos Domiciliarios – SUI de la Superintendencia de Servicios Públicos.*

43. **Infraestructuras para el desarrollo de actividades turísticas:** infraestructuras públicas disponibles que permitan la experiencia del turista y respondan a la vocación turística del destino. Ejemplo: torres de avistamiento de aves, senderos, señalización turística, entre otros.

Evaluación

CRITERIO	PUNTAJE
Cuenta con infraestructuras suficientes para el desarrollo de actividades turísticas y estas guardan relación con la vocación del municipio.	10
Cuenta parcialmente con infraestructuras que responden a la vocación turística del municipio.	5
El municipio **NO** cuenta con infraestructuras para el desarrollo de actividades turísticas.	0

Fuente de consulta: *documentación oficial de la alcaldía distrital o municipal.*
Anexo plantilla: *diligencie la plantilla incluyendo información asociada a las infraestructuras turísticas públicas del distrito o municipio.*

44. **Presupuesto asignado al funcionamiento y mantenimiento de la infraestructura para el turismo:** recursos asignados al funcionamiento y mantenimiento de las infraestructuras turísticas públicas que mejoran o posibilitan la experiencia del turista cuando llega al destino turístico.

Evaluación

CRITERIO	PUNTAJE
El municipio **SÍ** asignó recursos para el mantenimiento y funcionamiento de la infraestructura para el turismo.	10
El municipio **NO** asignó recursos para el mantenimiento y funcionamiento de la infraestructura para el turismo.	0

Fuente de consulta: *documentación oficial de la alcaldía distrital o municipal.*
Cuadro de información: *escriba en el cuadro el monto presupuestal asignado para el funcionamiento y mantenimiento de la infraestructura para el turismo en el último año (enero - diciembre).*

EVALUACIÓN DEL EJE
INFRAESTRUCTURA Y CONDICIONES BÁSICAS DEL DESTINO (15%)

Como resultado de la evaluación de los indicadores previamente descritos, se generará un puntaje para el eje "Infraestructura y condiciones básicas" que será calculado realizando la división de la sumatoria del total de los criterios ya evaluados en el eje en el número total de criterios, que para este caso es **21**. El resultado será multiplicado por **15%** que corresponde al peso porcentual del eje sobre el componente de oferta.

EJE 4
PLANTA TURÍSTICA

Además de atractivos e infraestructuras públicas, un destino turístico debe garantizar la prestación de servicios que faciliten la experiencia del visitante, permitiendo que este pueda realizar las actividades que le interesen bajo parámetros de calidad y accesibilidad.

A través de este eje se evalúan los principales indicadores asociados a la planta turística de un distrito o municipio. Una calificación superior en los indicadores incluidos en este eje, indica la existencia de condiciones posiblemente suficientes para la prestación de servicios turísticos, frente a la que tendrán que realizarse análisis asociados a la calidad y alcance, así como a la satisfacción que estos generan en la estadía del visitante.

45. **Cobertura en servicios de alojamiento y hospedaje:** relación entre el número de camas en establecimientos de alojamiento y hospedaje formales (con Registro Nacional de Turismo) y en funcionamiento, frente al número de turistas que visitan el distrito o municipio.

Evaluación

CRITERIO	PUNTAJE
El municipio o distrito cuenta con un porcentaje de cobertura en servicios de alojamiento y hospedaje mayor **que 80,1%**	10
El municipio o distrito cuenta con un porcentaje de cobertura en servicios de alojamiento y hospedaje entre **70,1% y 80%**	8
El municipio o distrito cuenta con un porcentaje de cobertura en servicios de alojamiento y hospedaje entre **50,1% y 70%**	6
El municipio o distrito cuenta con un porcentaje de cobertura en servicios de alojamiento y hospedaje entre **30,1% y 50%**	4
El municipio o distrito cuenta con un porcentaje de cobertura en servicios de alojamiento y hospedaje mayor que **0% y hasta 30%**	2
El municipio o distrito **NO** cuenta con servicios de alojamiento y hospedaje formalmente constituidos o **NO** realiza la medición de turistas.	0

Fuente de consulta: *Viceministerio de Turismo. Base de datos de Registro Nacional de Turismo.*
Cuadro de información: *escriba el porcentaje de cobertura que resultará de la siguiente fórmula: número de turistas nacionales y extranjeros que visitan el distrito o municipio/ número de camas en establecimientos de alojamiento y hospedaje formales y activos en el distrito o municipio * 100.*

46. **Servicios de agencias de viajes:** hace referencia a agencias de viajes que comercializan y operan la oferta turística del distrito o municipio.

Evaluación

CRITERIO	PUNTAJE
El distrito o municipio **SÍ** es comercializado y operado por agencias de viajes formalmente constituidas.	10
El distrito o municipio **NO** es comercializado y operado por agencias de viajes formalmente constituidas.	0

1. A partir de la segunda medición, el distrito o municipio tendrá que incluir un documento que contenga el número y clasificación (mayorista, minorista u operadora) de las agencias de viajes que comercializan y operan el destino de las que trata el artículo 16 de la Ley 1558.
2. Las agencias de viajes NO deben estar necesariamente ubicadas en el distrito o municipio, pero deben comercializar y operar la oferta turística del distrito o municipio.

Fuente de consulta: *información recopilada por el distrito o municipio.*

47. **Guías profesionales de turismo:** hace referencia al número de guías de turismo formales (con tarjeta profesional y Registro Nacional de Turismo) en el distrito o municipio.

Evaluación

CRITERIO	PUNTAJE
El distrito o municipio **SÍ** cuenta con guías profesionales de turismo.	10
El distrito o municipio **NO** cuenta con guías profesionales de turismo.	0

Fuente de consulta: *Viceministerio de Turismo. Base de datos de Registro Nacional de Turismo.*
Cuadro de información*: escriba el número de guías de turismo formales del distrito o municipio.*

48. **Servicios de establecimientos gastronómicos:** se entiende por establecimientos gastronómicos, bares y similares aquellos establecimientos comerciales en cabeza de personas naturales o jurídicas cuya actividad económica esté relacionada con la producción, servicio y venta de alimentos y bebidas para consumo. Además, podrán prestar otros servicios complementarios (Ley 300 de 1996, artículo 87).

Evaluación

CRITERIO	PUNTAJE
El distrito o municipio **SÍ** cuenta con establecimientos gastronómicos formales que atiendan la demanda turística.	10
El distrito o municipio **NO** cuenta con establecimientos gastronómicos formales que atiendan la demanda turística.	0

Fuente de consulta: *documentación propia del distrito o municipio.*
Cuadro de información*: escriba el número de establecimientos gastronómicos formales ubicados en el distrito o municipio.*

49. **Servicios de transporte terrestre turístico especial:** son aquellos que se prestan bajo la responsabilidad de una empresa de transporte legalmente constituida y debidamente habilitada en esta modalidad, a un grupo específico de personas ya sean estudiantes, turistas, empleados, personas con discapacidad y/o movilidad reducida, pacientes no crónicos y particulares, que requieren de un servicio expreso, siempre que hagan parte de un grupo determinable y de acuerdo con las condiciones y características que se definen en el Decreto (Decreto 348 de 2015).

Evaluación

CRITERIO	PUNTAJE
El distrito o municipio **SÍ** cuenta con servicios de transporte terrestre turístico especial.	10
El distrito o municipio **NO** cuenta con servicios de transporte terrestre turístico especial.	0

Fuente de consulta: *Viceministerio de Turismo. Base de datos de Registro Nacional de Turismo.*
Cuadro de información*: escriba el número de empresas de transporte turístico terrestre especial formales, que operan en el distrito o municipio.*

EVALUACIÓN FINAL
PLANTA TURÍSTICA (15%)

Como resultado de la evaluación de los indicadores previamente descritos, se generará un puntaje para el eje "Planta turística" que será calculado realizando la división de la sumatoria del total de los criterios ya evaluados en el eje en el número total de criterios, que para este caso es **5**. El resultado será multiplicado por **15%** que corresponde al peso porcentual del eje sobre el componente de oferta.

EJE 5
FORMACIÓN Y CAPACITACIÓN EN TURISMO (10%)

En el proceso de desarrollo turístico es fundamental contar con personas que cuenten con los requisitos de formación y capacitación necesarios para garantizar al turista una experiencia de calidad. La formación hace referencia a un proceso de mediana o larga duración y varios niveles, que incluye el desarrollo de un programa en una disciplina de forma amplia. Por su parte, la capacitación consiste en un proceso educativo de corta duración que otorga conocimientos y habilidades puntuales técnicas para ejecutar tareas en el ámbito laboral.

Entendiendo lo anterior, es fundamental contar con personas capacitadas en diferentes niveles y temáticas, que cuenten con las habilidades necesarias para responder de forma oportuna a los retos del sector. Así mismo, es necesario que quienes se encuentran interesados en vincularse laboralmente al sector, encuentren una oferta de programas que responda a las necesidades de los empleadores y exigencias de la actividad turística.

A través de este eje se evalúan los principales indicadores asociados a procesos de formación y capacitación en turismo. Una calificación superior en los indicadores incluidos en este eje, refleja la importancia que el destino otorga a la profesionalización del sector, así como a la contratación de talento humano competente.

50. **Colegios Amigos del Turismo:** programa del Viceministerio de Turismo que busca acercar e integrar a las instituciones educativas públicas del país al desarrollo turístico nacional, a través de procesos de sensibilización, formación y participación que fortalezcan la apropiación del territorio, la comprensión de la transversalidad de la actividad, la conservación del patrimonio natural y cultural y la profesionalización del sector.

El programa propende por la construcción de tejido social y propone el estudio de la actividad turística como alternativa profesional, permitiendo que una vez los estudiantes finalicen su formación académica básica y media, encuentren en el turismo una posibilidad de desarrollo académico, vocacional y laboral.

Evaluación

CRITERIO	PUNTAJE
El municipio o distrito cuenta con un porcentaje mayor que **15%** de instituciones educativas **vinculadas al programa de Colegios Amigos del Turismo,** sobre el total de las instituciones de educación pública.	10
El municipio o distrito cuenta con un porcentaje mayor que **0% y hasta 15%** de instituciones educativas **vinculados al programa de Colegios Amigos del Turismo,** sobre el total de las instituciones de educación pública.	5
El municipio o distrito **NO** cuenta con **Colegios Amigos del Turismo.**	0

1. El porcentaje resultará de la siguiente fórmula de cálculo: (número de instituciones de educación pública vinculadas al programa de Colegios Amigos del Turismo / número total de instituciones de educación pública del distrito o municipio) x 100.

Fuente de consulta: *Viceministerio de Turismo (número de Colegios Amigos del Turismo por municipio) y registro de instituciones de educación pública por municipio.*

51. **Programas de pregrado activos en los niveles técnico y tecnológico en turismo:** programas de pregrado activos en los niveles técnico y tecnológico, cuyos contenidos responden a las necesidades de formación del sector turístico (hotelería, turismo, guionaje, eventos, gastronomía y bares).

Evaluación

CRITERIO	PUNTAJE
El departamento al que pertenece el distrito o municipio cuenta con un porcentaje **igual o mayor a 5,64% de programas de pregrado en turismo activos en los niveles técnico y tecnológico**, sobre el total de programas de pregrado en los niveles técnico y tecnológico, disponibles en el departamento.	10
El departamento al que pertenece el distrito o municipio cuenta con un porcentaje **entre el 4,23% y 5,63% de programas de pregrado en turismo activos en los niveles técnico y tecnológico,** sobre el total de programas de pregrado en los niveles técnico y tecnológico, disponibles en el departamento.	8
El departamento al que pertenece el distrito o municipio cuenta con un porcentaje **entre el 2,82% y 4,22% de programas de pregrado en turismo activos en los niveles técnico y tecnológico**, sobre el total de programas de pregrado en los niveles técnico y tecnológico, disponibles en el departamento.	6
El departamento al que pertenece el distrito o municipio cuenta con un porcentaje **entre el 1,41% y 2,81% de programas de pregrado en turismo activos en los niveles técnico y tecnológico,** sobre el total de programas de pregrado en los niveles técnico y tecnológico, disponibles en el departamento.	4
El departamento al que pertenece el distrito o municipio cuenta con un porcentaje **mayor que 0% y hasta 1,40% de programas de pregrado en turismo activos en los niveles técnico y tecnológico,** sobre el total de programas de pregrado en los niveles técnico y tecnológico, disponibles en el departamento.	2
El departamento al que pertenece el municipio **NO** cuenta con **programas de pregrado activos en los niveles técnico y tecnológico, que respondan a las necesidades del sector turístico.**	0

1. Este indicador evaluará información a nivel departamental.
2. Si bien se adjunta la base de información por departamentos, se recomienda verificar en el Sistema Nacional de Información de la Educación Superior los programas **ACTIVOS** *en los niveles técnico y tecnológico cuyos contenidos respondan a las necesidades de formación del sector turístico.*
*3. La fórmula de cálculo empleada para este indicador será: (número de programas de pregrado en turismo activos, en los niveles técnico y tecnológico en el departamento/número de programas de pregrado activos en los niveles técnico y tecnológico en el departamento) *100.*

Fuente de consulta: *base de datos programas de formación técnica y tecnológica en turismo (departamental) y Sistema Nacional de Información de la Educación Superior (identificar los programas de formación activos en los niveles técnico y tecnológico cuyos contenidos respondan a las necesidades de formación del sector turístico).*

52. Programas de pregrado en nivel profesional para el sector turismo: programas de pregrado activos en nivel profesional, cuyos contenidos responden a las necesidades de formación del sector turístico (hotelería, turismo, guionaje, eventos, gastronomía y bares).

Evaluación

CRITERIO	PUNTAJE
El departamento al que pertenece el distrito o municipio cuenta con un porcentaje igual o mayor a **4% de programas de pregrado en turismo activos en nivel profesional,** sobre el total de programas de pregrado en nivel profesional, disponibles en el departamento.	10
El departamento al que pertenece el distrito o municipio cuenta con un porcentaje entre el **3% y 3,99% de programas de pregrado en turismo activos en nivel profesional,** sobre el total de programas de pregrado en nivel profesional, disponibles en el departamento.	8
El departamento al que pertenece el distrito o municipio cuenta con un porcentaje entre el **2% y 2,99% de programas de pregrado en turismo activos en nivel profesional,** sobre el total de programas de pregrado en nivel profesional, disponibles en el departamento.	6
El departamento al que pertenece el distrito o municipio cuenta con un porcentaje entre el **1% y 1,99% de programas de pregrado en turismo activos en nivel profesional,**	4

sobre el total de programas de pregrado en nivel profesional, disponibles en el departamento.	
El departamento al que pertenece el distrito o municipio cuenta con un porcentaje mayor que **0% y hasta 0,99% de programas de pregrado en turismo activos en nivel profesional,** sobre el total de programas de pregrado en nivel profesional, disponibles en el departamento.	2
El departamento al que pertenece el distrito o municipio **NO** cuenta con **programas de pregrado activos que responden a las necesidades del sector turístico.**	0

1. Este indicador evaluará información a nivel departamental.

*2. Si bien se adjunta la base de información por departamentos, se recomienda verificar en el Sistema Nacional de Información de la Educación Superior los programas **ACTIVOS** en nivel profesional cuyos contenidos respondan a las necesidades de formación del sector turístico.*

*3. La fórmula de cálculo empleada para este indicador será: (número de programas de pregrado en turismo activos en nivel profesional en el departamento/número de programas de pregrado activos en nivel profesional en el departamento) *100.*

Fuente de consulta: *base de datos programas de formación profesional en turismo (departamental) y Sistema Nacional de Información de la Educación Superior (identificar los programas de formación en nivel profesional cuyos contenidos respondan a las necesidades de formación del sector turístico).*

53. **Programas de posgrado en turismo:** programas de posgrado activos en los niveles de especialización tecnológica, especialización universitaria, maestría o doctorado, cuyos contenidos responden a las necesidades de formación del sector turístico.

Evaluación

CRITERIO	PUNTAJE
El departamento al que pertenece el municipio cuenta con un porcentaje igual o mayor a **1,93% de programas de posgrado activos en turismo,** sobre el total de programas de posgrado disponibles en el departamento.	10
El departamento al que pertenece el municipio cuenta con un porcentaje mayor que **0% y hasta 1,92% de programas de posgrado activos en turismo,** sobre el total de programas de posgrado disponibles en el departamento.	5
El departamento al que pertenece el municipio **NO** cuenta con **programas de posgrado activos que respondan a las necesidades del sector turístico.**	0

1. Este indicador evaluará información a nivel departamental.

2. Si bien se adjunta la base de información por departamentos, se recomienda verificar en el Sistema Nacional de Información de la Educación Superior los programas ***ACTIVOS*** *de posgrado cuyos contenidos respondan a las necesidades de formación del sector turístico.*

*3. La fórmula de cálculo empleada para este indicador será: (número de programas de posgrado en turismo, activos en el departamento/número de programas de posgrado activos en el departamento) *100.*

Fuente de consulta: *base de datos programas de formación profesional en turismo (departamental) y Sistema Nacional de Información de la Educación Superior (identificar los programas de posgrado activos, cuyos contenidos respondan a las necesidades de formación del sector turístico).*

54. **Bilingüismo en programas de pregrado en los niveles técnico y tecnológico para el sector turismo:** formación en un segundo idioma (diferente a español) en programas de pregrado en turismo de nivel técnico o tecnológico.

Evaluación

CRITERIO	PUNTAJE
El departamento al que pertenece el distrito o municipio cuenta con un porcentaje **mayor que 50%** de formación bilingüe en programas de pregrado en los niveles técnico y tecnológico para el sector turismo.	10
El departamento al que pertenece el distrito o municipio cuenta con un porcentaje **mayor que 0% y hasta el 50%** de formación bilingüe en programas de pregrado en los niveles técnico y tecnológico para el sector turismo.	5
El departamento al que pertenece el distrito o municipio **NO** cuenta con formación bilingüe en programas de pregrado en los niveles técnico y tecnológico para el sector turismo.	0

1. Este indicador evaluará información a nivel departamental.
2. Si bien se adjunta la base de información por departamentos, se recomienda contrastar la información con el pensum de cada institución educativa. En caso de identificar datos que deban ser modificados, por favor comunicar esta situación al gestor territorial a cargo.
3. Consultar la columna "J" del archivo de consulta.

Fuente de consulta: *base de datos de programas de pregrado en los niveles técnico y tecnológico con formación bilingüe (departamental).*

55. Bilingüismo en programas de pregrado en nivel profesional para el sector turismo: formación en un segundo idioma (diferente a español) en programas de pregrado en turismo de nivel profesional.

Evaluación

CRITERIO	PUNTAJE
El departamento al que pertenece el distrito o municipio cuenta con un porcentaje **mayor que 50%** de formación bilingüe en programas de pregrado en nivel profesional para el sector turismo.	10
El departamento al que pertenece el distrito o municipio cuenta con un porcentaje **mayor que 0% y hasta el 50%** de formación bilingüe en programas de pregrado en nivel profesional para el sector turismo.	5
El departamento al que pertenece el distrito o municipio **NO** cuenta con formación bilingüe en programas de pregrado en nivel profesional para el sector turismo.	0

1. Este indicador evaluará información a nivel departamental.
2. Si bien se adjunta la base de información por departamentos, se recomienda contrastar la información con el pensum de cada institución educativa. En caso de identificar datos que deban ser modificados, por favor comunicar esta situación al gestor territorial a cargo.
3. Consultar la columna "J" del archivo de consulta.

Fuente de consulta: *base de datos de programas de pregrado en nivel profesional con formación bilingüe (departamental).*

56. **Educación no formal en turismo:** articulación del gobierno distrital o municipal para la generación y fortalecimiento de capacidades de los actores de la cadena del sector turístico. La educación no formal hace referencia a "todo conocimiento libre y espontáneamente adquirido, proveniente de personas, entidades, medios masivos de comunicación, medios impresos, tradiciones, costumbres, comportamientos sociales y otros no estructurados" (Ley 115 de1994).

Evaluación

CRITERIO	PUNTAJE
El distrito o municipio **SÍ** gestiona el desarrollo de procesos de educación no formal para el sector turismo.	10
El distrito o municipio **NO** gestiona el desarrollo de procesos de educación no formal para el sector turismo.	0

1. Este indicador evaluará información a nivel distrital o municipal.

Fuente de consulta: *documentación oficial de la alcaldía distrital o municipal.*
Anexo plantilla: *incluya la información asociada a los procesos de educación no formal en turismo adelantados por el distrito o municipio durante los últimos 12 meses.*

EVALUACIÓN FINAL
FORMACIÓN Y CAPACITACIÓN EN TURISMO (10%)

Como resultado de la evaluación de los indicadores previamente descritos, se generará un puntaje para el eje "Formación y capacitación en turismo" que será calculado realizando la división de la sumatoria del total de los criterios ya evaluados en el eje en el número total de criterios, que para este caso es **7**. El resultado será multiplicado por **10%** que corresponde al peso porcentual del eje sobre el componente de oferta.

EJE 6.
PRODUCTO TURÍSTICO

El producto turístico, hace referencia a la combinación de elementos a los que accede el turista en el desarrollo de su experiencia de viaje (atractivos, infraestructuras, servicios y actividades), los cuales en conjunto satisfacen sus motivaciones y necesidades.

Realizar un ejercicio de diseño de producto turístico se constituye como el primer paso para adelantar actividades que respondan a la vocación territorial y sean coherentes con las políticas y lineamientos de planificación definidos a nivel distrital o municipal, departamental, regional y nacional. Así mismo, el compromiso y dedicación de parte de los actores de la cadena de valor en el ejercicio de implementación y sostenibilidad del producto serán aspectos fundamentales, garantizando el desarrollo de experiencias de calidad, responsables y competitivas.

A través de este eje se evalúan los principales indicadores asociados al diseño e implementación de productos turísticos, así como algunos de los elementos más importantes para este ejercicio asociados a la vocación territorial, el estado de atractivos y recursos y su vínculo a uno o más productos turísticos a nivel distrital o municipal. Una calificación superior en los indicadores incluidos en este eje, refleja la importancia que el destino otorga al desarrollo de experiencias turísticas bajo criterios de sostenibilidad, responsabilidad y coherencia.

57. **Inventario de recursos y atractivos turísticos:** herramienta que permite el registro de la información de recursos y atractivos turísticos de un destino que, por sus características, motivan o podrían motivar el desplazamiento de flujos turísticos. Este documento incluirá información relacionada con el estado de los bienes turísticos con los que cuenta un municipio.

Evaluación

CRITERIO	PUNTAJE
El municipio **SÍ** cuenta con un inventario turístico documentado bajo la metodología definida por el Viceministerio de Turismo (fecha de levantamiento o actualización NO mayor a tres años).	10
El municipio **SÍ** cuenta con un inventario turístico documentado bajo la metodología definida por el Viceministerio de Turismo (fecha de levantamiento o actualización mayor a tres años).	8
El municipio **SÍ** cuenta con un inventario turístico documentado bajo una metodología DIFERENTE a la definida por el Viceministerio de Turismo (fecha del documento NO mayor a tres años).	6
El municipio **SÍ** cuenta con un inventario turístico documentado bajo una metodología DIFERENTE a la definida por el Viceministerio de Turismo (fecha del documento mayor a tres años).	4
El municipio **NO** cuenta con un inventario turístico o cuenta con un inventario con fecha de levantamiento o actualización mayor a tres años.	2

Fuente de consulta: *Viceministerio de Turismo (distritos o municipios de Corredores Turísticos) o documentación oficial de la alcaldía distrital o municipal.*
Anexo: *distritos o municipios que pertenecen a la estrategia de Corredores Turísticos: no será necesario adjuntar ningún documento, teniendo en cuenta que el Viceministerio de Turismo cuenta con la información del proyecto FNT 068 de 2017. Distritos o municipios que NO pertenecen a la estrategia de Corredores Turísticos: documento de inventario turístico bajo la metodología del Viceministerio de Turismo u otra metodología realizada por el municipio".*

58. **Estructuración del producto turístico:** hace referencia al ejercicio de estructuración de la oferta que incluye un conjunto de bienes y servicios dispuestos para el consumo turístico, asociados a actividades de naturaleza, cultural, sol y playa, reuniones, náutico y cruceros, aventura, salud y bienestar; que satisfacen las necesidades y expectativas del visitante.

Evaluación

CRITERIO	PUNTAJE
El distrito o municipio cuenta con uno o más documentos de diseño de producto turístico implementados.	10
El distrito o municipio cuenta con uno o más documentos de diseño de producto turístico en etapa de implementación.	8
El distrito o municipio cuenta con uno o más documentos de diseño de producto turístico sin implementar.	6
El distrito o municipio cuenta con uno o más productos turísticos que actualmente son comercializados, pero **NO** fue o fueron desarrollados a través de un documento de diseño de producto turístico.	4
El municipio **SÍ** ha adelantado actividades para la identificación del producto turístico.	2
El municipio **NO** ha adelantado procesos para la identificación del producto turístico.	0

Fuente de consulta: *documentación oficial del distrito o municipio.*
Anexo: *en caso de calificar el criterio con 10, 8 o 6, adjuntar documento de diseño de producto turístico. En caso de calificar el criterio con 2, adjuntar los soportes de las actividades para la identificación del producto turístico.*

59. **Destino priorizado en los planes estratégicos de naturaleza, cultura, MICE o salud y bienestar:** el Viceministerio de Turismo ha priorizado cuatro tipologías que responden al potencial turístico nacional (naturaleza, cultura, MICE y salud y bienestar). Para garantizar su desarrollo organizado y coherente, el Viceministerio de Turismo cuenta con un plan estratégico para cada uno de estos segmentos, que a su vez priorizan destinos con potencial para el desarrollo de productos turísticos.

Evaluación

CRITERIO	PUNTAJE
El distrito o municipio **SÍ** se encuentra priorizado en al menos uno de los planes estratégicos de naturaleza, cultura, MICE y salud y bienestar **Y** ha adelantado las acciones definidas en estos instrumentos.	10
El distrito o municipio **SÍ** se encuentra priorizado en al menos uno de los planes estratégicos de naturaleza, cultura, MICE y salud y bienestar.	5
El distrito o municipio **NO** se encuentra priorizado en ninguno de los planes estratégicos de naturaleza, cultura, MICE y salud y bienestar.	0

Fuente de consulta: *Plan de negocios de turismo de naturaleza, Plan estratégico y de negocios del turismo cultural de Colombia, Plan estratégico nacional para el desarrollo del turismo MICE en Colombia y Plan de negocios para el subsector de turismo de bienestar en Colombia.*

60. **Bienes del patrimonio cultural (material, inmaterial, festividades y eventos y grupos de especial interés) en el producto turístico:** recursos y atractivos identificados en los inventarios turísticos en la categoría de patrimonio cultural vinculados a los productos turísticos operados y comercializados por agencias de viajes.

Evaluación

CRITERIO	PUNTAJE
El distrito o municipio cuenta un porcentaje mayor que **80%** de bienes del patrimonio cultural operados y comercializados por agencias de viajes.	10
El distrito o municipio cuenta un porcentaje entre **60,01% y hasta el 80%** de bienes del patrimonio cultural operados y comercializados por agencias de viajes.	8
El distrito o municipio cuenta un porcentaje entre **40,01% y hasta el 60%** de bienes del patrimonio cultural operados y comercializados por agencias de viajes.	6
El distrito o municipio cuenta un porcentaje entre **20,01% y hasta el 40%** de bienes del patrimonio cultural operados y comercializados por agencias de viajes.	4
El distrito o municipio cuenta un porcentaje **mayor a 0% y hasta el 20%** de bienes del patrimonio cultural operados y comercializados por agencias de viajes.	2
El distrito o municipio **NO** cuenta con bienes de patrimonio cultural operados y comercializados por agencias de viajes.	0

1. Filtrar la casilla "I" seleccionando "Patrimonio cultural" y la casilla "C" seleccionando su municipio en el documento "Inventarios turísticos_2020".

Fuente de consulta: *documentación oficial del distrito o municipio e inventario de recursos y atractivos turísticos.*
Cuadro de información*: emplear la siguiente fórmula de cálculo: (número de recursos y atractivos en la categoría de patrimonio cultural, vinculados a paquetes turísticos actualmente operados y comercializados / número de recursos y atractivos bajo la categoría de patrimonio cultural incluidos en el inventario turístico)*100.*

61. **Bienes de patrimonio natural en el producto turístico:** recursos y atractivos identificados en los inventarios turísticos en la categoría de patrimonio natural vinculados a los productos turísticos operados y comercializados por agencias de viajes.

Evaluación

CRITERIO	PUNTAJE
El distrito o municipio cuenta un porcentaje mayor que **80%** de bienes del patrimonio natural operados y comercializados por agencias de viajes.	10
El distrito o municipio cuenta un porcentaje entre **60,01% y hasta el 80%** de bienes del patrimonio natural operados y comercializados por agencias de viajes.	8
El distrito o municipio cuenta un porcentaje entre **40,01% y hasta el 60%** de bienes del patrimonio natural operados y comercializados por agencias de viajes.	6
El distrito o municipio cuenta un porcentaje entre **20,01% y hasta el 40%** de bienes del patrimonio natural operados y comercializados por agencias de viajes.	4
El distrito o municipio cuenta un porcentaje **mayor a 0% y hasta el 20%** de bienes del patrimonio natural operados y comercializados por agencias de viajes.	2
El distrito o municipio **NO** cuenta con bienes de patrimonio natural operados y comercializados por agencias de viajes.	0

1. *Filtrar la casilla "I" seleccionando "Patrimonio natural" y la casilla "C" seleccionando su municipio en el documento "Inventarios turísticos_2020".*

Fuente de consulta: *documentación oficial del distrito o municipio e inventario de recursos y atractivos turísticos.*

Cuadro de información*: emplear la siguiente fórmula de cálculo: (número de recursos y atractivos en la categoría de patrimonio cultural, vinculados a paquetes turísticos actualmente operados y comercializados / número de recursos y atractivos bajo la categoría de patrimonio cultural incluidos en el inventario turístico)*100.*

EVALUACIÓN FINAL
PRODUCTO TURÍSTICO (10%)

Como resultado de la evaluación de los indicadores previamente descritos, se generará un puntaje para el eje "Producto turístico" que será calculado realizando la división de la sumatoria del total de los criterios ya evaluados en el eje en el número total de criterios, que para este caso es **5**. El resultado será multiplicado por **10%** que corresponde al peso porcentual del eje sobre el componente de oferta.

EJE 7.
PROMOCIÓN Y COMERCIALIZACIÓN

El concepto de promoción turística abarca aquellas acciones necesarias para dar a conocer la oferta de un territorio, fortalecer su identidad hacia los actores de destino, los turistas y otros destinos; así como atraer nuevos viajeros que se encuentren interesados en consumir la oferta promocionada. Para el caso colombiano, estas actividades deben estar enmarcadas en los lineamientos de la Política Nacional de Mercadeo y Promoción Turística.

Si bien las actividades de mercadeo y promoción adquieren gran importancia por su impacto en la atracción de turistas e inversiones, se hace necesario que los destinos tengan plena conciencia del proceso de desarrollo turístico, con el fin de garantizar que los recursos distritales o municipales se inviertan de forma coherente en las necesidades de los territorios y así evitar impactos negativos que a mediano y largo plazo afecten la sostenibilidad de los destinos.

Para adelantar actividades de promoción y mercadeo turístico, a través de la Política Nacional de Mercadeo y Promoción Turística, el Viceministerio de Turismo determina las siguientes pautas de trabajo:

- El desarrollo de investigaciones de mercados, al igual que la innovación, representan herramientas imprescindibles para competir en entornos económicos internacionales, en donde las tendencias de consumo de los turistas nacionales e internacionales marcan la pauta de la demanda de productos que conforman la oferta del sector.
- El mercadeo y la promoción de los destinos turísticos debe apoyar el desarrollo de nuevos productos turísticos, así como el mantenimiento de los ya existentes. Esto permitirá al país captar nuevos segmentos de mercado potenciales y conservar la demanda actual, especialmente la doméstica.
- Las actividades de promoción que se adelanten deberán garantizar su propósito de efectividad y demostrar que los mercados emisores donde estas se adelanten tengan potencial claramente identificado y estudiado previamente.

- Es necesario apoyar la definición y estructuración de mecanismos de comercialización que faciliten el acceso de los productos y destinos a los mercados, dando mayor impulso a la transformación de los procesos de comercialización, otorgándole mayor relevancia a la relación con el cliente y a la adecuación constante ante los nuevos modelos y espacios de comunicación propios de los procesos tecnológicos, tales como las nuevas TIC. Esto permite el logro de un análisis efectivo de los segmentos de mercado y de las realidades y tendencias de la cadena de valor de cada producto turístico.

A través de este eje se evalúan los principales indicadores asociados al desarrollo de procesos de promoción y comercialización turística. Una calificación superior en los indicadores incluidos en este eje evidencia los esfuerzos distritales o municipales en la identificación de mercados, la promoción de los productos y destinos y su comercialización

62. **Plan de mercadeo y promoción:** herramienta que permite la definición de acciones para el desarrollo y fortalecimiento del mercadeo y la promoción de los destinos, definiendo productos y segmentos o perfiles de los turistas, de acuerdo con la estrategia de mercadeo nacional o internacional que defina el destino.

Evaluación

CRITERIO	PUNTAJE
El distrito o municipio **SÍ** cuenta con un plan de mercadeo y promoción.	10
El distrito o municipio **NO** cuenta con un plan de mercadeo y promoción.	0

Fuente de consulta: *documentación oficial del distrito o municipio.*
Anexo: *documento que corresponda al "plan de mercadeo y promoción" distrital o municipal.*

63. **Recursos asignados a la promoción y comercialización turística:** recursos asignados a actividades que permitan la promoción y comercialización turística distrital o municipal. Entiéndase como promoción y comercialización actividades relacionadas con campañas, marca, fam trips, press trips, participación en ruedas de negocios y ferias nacionales e internacionales, entre otros.

Evaluación

CRITERIO	PUNTAJE
El distrito o municipio **SÍ** asignó recursos a la promoción y comercialización turística.	10
El distrito o municipio **NO** asignó recursos a la promoción y comercialización turística.	0

Fuente de consulta: *documentación oficial de la alcaldía municipal o distrital.*

***Cuadro de información**: escriba el valor total de recursos asignados para el desarrollo de actividades de promoción y comercialización a nivel distrital o municipal en la vigencia anterior a la implementación de esta metodología (Ej. 2020).*

64. **Vinculación del distrito o municipio en campañas de promoción turística:** conjunto de acciones que permiten conceptualizar, diseñar y comunicar la oferta turística de un destino a través de la definición de prioridades, canales y segmentos que respondan a los objetivos territoriales y se enmarquen en los lineamientos nacionales y regionales.

Evaluación

CRITERIO	PUNTAJE
El distrito o municipio ha estado vinculado a campañas de promoción turística **INTERNACIONAL** en los últimos dos años.	10
El distrito o municipio ha estado vinculado a campañas de promoción turística **NACIONAL** en los últimos dos años.	8
El distrito o municipio ha estado vinculado a campañas de promoción turística **REGIONAL** en los últimos dos años.	6
El distrito o municipio ha estado vinculado a campañas de promoción turística **DEPARTAMENTAL** en los últimos dos años.	4
El distrito o municipio ha estado vinculado a campañas de promoción turística **MUNICIPAL** en los últimos dos años.	2
El distrito o municipio **NO** ha estado vinculado a campañas de promoción turística en los últimos dos años.	0

***Fuente de consulta:** documentación oficial de la alcaldía municipal o distrital.*
***Anexo:** listado de campañas de promoción turística en las que está vinculado el municipio (nivel, año y nombre de la campaña) en los últimos dos años.*

65. **Participación en ferias de turismo:** eventos de carácter público que tienen como objetivo principal la presentación, difusión y comercialización de la oferta turística de

un destino, así como el desarrollo de negocios, alianzas e investigaciones. Las ferias de turismo pueden ser de carácter internacional, nacional o regional.

Evaluación

CRITERIO	PUNTAJE
El distrito o municipio **SÍ** ha participado en ferias nacionales e internacionales de turismo en los últimos cuatro años.	10
El distrito o municipio ha participado **ÚNICAMENTE** en ferias nacionales de turismo en los últimos cuatro años.	5
El distrito o municipio **NO** ha participado en ferias de turismo en los últimos cuatro años.	0

Fuente de consulta: *documentación oficial de la alcaldía municipal.*
Anexo: *listado de ferias en las que ha participado el distrito o municipio con su respectivo año. Información asociada máximo a los últimos cuatro (4) años.*

EVALUACIÓN FINAL
PROMOCIÓN Y COMERCIALIZACIÓN (10%)

Como resultado de la evaluación de los indicadores previamente descritos, se generará un puntaje para el eje "Promoción y comercialización" que será calculado realizando la división de la sumatoria del total de los criterios ya evaluados en el eje en el número total de criterios, que para este caso es **4**. El resultado será multiplicado por **10%** que corresponde al peso porcentual del eje sobre el componente de oferta.

DEMANDA

EJE 8.
DEMANDA NACIONAL

El análisis de la demanda adquiere gran importancia por su impacto en el desarrollo turístico de un destino a través del reconocimiento de las características de quien se interesa en él. Las llegadas por turismo y la información generada alrededor de la complejidad del turista, sus motivaciones, expectativas y necesidades, permite asegurar en buena parte la sostenibilidad económica de los destinos, a partir del mejoramiento de la calidad en la prestación de servicios, permitiendo además la diversificación de productos y servicios, el incremento de las visitas por turismo y mayor adaptación a los cambios de la demanda.

Sumado a esto, el conocimiento de la demanda permite a los destinos definir los límites y parámetros para el desarrollo de la actividad turística desde la óptica de inversionistas, prestadores de servicios turísticos, proveedores y turistas (en este caso nacionales); propiciando que el turismo se desarrolle en términos de sostenibilidad social, cultural y ambiental a largo plazo; contribuyendo además, al diseño de estrategias efectivas de diferenciación y segmentación, diseño de producto, fortalecimiento empresarial, innovación y comercialización; así como la ejecución de inversiones responsables y coherentes con las necesidades territoriales y las metas sectoriales.

La demanda nacional representa los ingresos por turismo de un amplio número de destinos de Colombia; sin embargo, no es frecuente priorizar el análisis de la demanda frente a los ejercicios de diseño de producto turístico. Este eje pretende generar un primer acercamiento de los destinos a los aspectos más relevantes de la demanda, con el fin de identificar las necesidades en investigación de mercados y estructuración de mediciones que sean necesarias para la toma de decisiones de cara al turismo doméstico.

66. Ingreso de visitantes nacionales al municipio: número de visitantes *nacionales* (excursionistas y turistas) que ingresan al distrito o municipio provenientes desde de su lugar de residencia u otro destino, por una duración inferior a un año y por motivos personales, profesionales o de negocios.

Evaluación

CRITERIO	PUNTAJE
El municipio **SÍ** realizó la medición del número de visitantes nacionales que ingresaron el año pasado.	10
El municipio **EVENTUALMENTE** realiza la medición del número de visitantes nacionales que recibe (temporadas altas, ferias y eventos, otras actividades).	5
El municipio **NO** realiza medición del número de visitantes nacionales que recibe.	0

Fuente de consulta: *documentación oficial del distrito o municipio.*
Cuadro de información*: escriba el número exacto de visitantes NACIONALES (excursionistas y turistas) que ingresaron al distrito o municipio en el año anterior a la implementación de esta metodología. Ejemplo: enero de 2020 a diciembre de 2020.*

67. Variación en la llegada de visitantes nacionales al municipio: la relación en porcentaje entre el número de visitantes *nacionales* recibidos durante el último año, respecto al número de visitantes *nacionales* reportado en el año inmediatamente anterior.

Evaluación

CRITERIO	PUNTAJE
El distrito o municipio reporta una variación por **ENCIMA** del crecimiento o por **DEBAJO** del descenso en la llegada de visitantes nacionales (su resultado es mejor que la base de evaluación).	10
El distrito o municipio reporta una variación **IGUAL** al crecimiento o descenso en la llegada de visitantes nacionales (su resultado es igual que la base de evaluación).	6

El distrito o municipio reporta una variación por **DEBAJO** del crecimiento o por **ENCIMA** del descenso en la llegada de visitantes nacionales (su resultado es peor que la base de evaluación).	2
El distrito o municipio **NO** cuenta con información suficiente para determinar la variación de la llegada de visitantes nacionales.	0

Fuente de consulta: *sistemas de información turística distritales o municipales. Documentación oficial de la alcaldía distrital o municipal.*
Cuadro de información: *hacer uso de la siguiente fórmula: ((número de visitantes nacionales del año 2 (2020) – número de visitantes nacionales del año 1 (2019)) /año 1 (2019)) *100*

Se toma como referencia el porcentaje de incremento o descenso de visitantes de acuerdo con las cifras del Ministerio de Comercio, Industria y Turismo, como valor máximo para el crecimiento o disminución del número de visitantes. Esta referencia variará según las cifras que presente el Ministerio de Comercio, Industria y Turismo cada año.

68. Procedencia de los mercados nacionales potenciales: identificación del origen de los visitantes nacionales (departamentos) que ingresan al municipio.

Evaluación

CRITERIO	PUNTAJE
El municipio **SÍ** identifica la procedencia de los mercados nacionales potenciales.	10
El municipio **NO** identifica la procedencia de los mercados nacionales potenciales.	0

Fuente de consulta: *Sistemas de información turística distritales o municipales y documentación oficial de la alcaldía distrital o municipal.*
Cuadro de información: *escriba el texto de los TRES departamentos que corresponden a la procedencia de los visitantes nacionales que ingresan al municipio.*

69. Conectividad aérea nacional (porcentaje de ocupación de sillas aéreas en vuelos nacionales): hace referencia al número de asientos ocupados por pasajeros, sobre el número de sillas disponibles para la venta. Incluye los asientos ya vendidos en una etapa de vuelo como los ocupados por pasajeros en tránsito, pero excluye los asientos que no estén realmente disponibles para el transporte de pasajeros debido a límites del peso bruto máximo de operación.

Evaluación

CRITERIO	PUNTAJE
El porcentaje de ocupación promedio en vuelos nacionales para el departamento está entre **80,1% y 100%**	10
El porcentaje de ocupación promedio en vuelos nacionales para el departamento está entre **60,1% y 80%**	8
El porcentaje de ocupación promedio en vuelos nacionales para el departamento está entre **40,1% y 60%**	6
El porcentaje de ocupación promedio en vuelos nacionales para el departamento está entre **20,1% y 40%**	4
El porcentaje de ocupación promedio en vuelos nacionales para el departamento es mayor que **0% y hasta 20%**	2
No aplica para el departamento.	5*

1. Este indicador evaluará información a nivel departamental.
2. Hace referencia a vuelos nacionales.

Fuente de consulta: *Aeronáutica Civil de Colombia. Tráfico Equipo. [Base de datos]. Corte primer trimestre 2020. Recuperado de http://www.aerocivil.gov.co/atencion/estadisticas-de-las-actividades-aeronauticas/bases-de-datos*
Base porcentaje de ocupación promedio en vuelos nacionales.
Cuadro de información: *indique el nombre del aeropuerto seleccionado como principal receptor de de vuelos nacionales con visitantes que se dirigen al distrito o municipio (entiéndase como "principal" el aeropuerto más utilizado por los turistas para llegar al distrito o municipio, aunque deban utilizar otros medios de transporte para llegar al destino).*

EVALUACIÓN DEL EJE DEMANDA NACIONAL (20%)

Como resultado de la evaluación de los indicadores previamente descritos, se generará un puntaje para el eje "Demanda nacional" que será calculado realizando la división de la sumatoria del total de los criterios ya evaluados en el eje en el número total de criterios, que para este caso es **4**. El resultado será multiplicado por **20%** que corresponde al peso porcentual del eje sobre el componente de demanda.

EJE 9.
DEMANDA INTERNACIONAL

El análisis de la demanda adquiere gran importancia por su impacto en el desarrollo turístico de un destino a través del reconocimiento de las características de quien se interesa en él. Las llegadas por turismo y la información generada alrededor de la complejidad del turista, sus motivaciones, expectativas y necesidades, permite asegurar en buena parte la sostenibilidad económica de los destinos, a partir del mejoramiento de la calidad en la prestación de servicios, permitiendo además la diversificación de productos y servicios, el incremento de las visitas por turismo y mayor adaptación a los cambios de la demanda.

Sumado a esto, el conocimiento de la demanda permite a los destinos definir los límites y parámetros para el desarrollo de la actividad turística desde la óptica de inversionistas, prestadores de servicios turísticos, proveedores y turistas (en este caso extranjeros); propiciando que el turismo se desarrolle en términos de sostenibilidad social, cultural y ambiental a largo plazo; contribuyendo además, al diseño de estrategias efectivas de diferenciación y segmentación, diseño de producto, fortalecimiento empresarial, innovación y comercialización; así como la ejecución de inversiones responsables y coherentes con las necesidades territoriales y las metas sectoriales.

La demanda internacional representa los ingresos por turismo de productos y servicios que han logrado dar respuesta a las motivaciones de turistas extranjeros; sin embargo, como en la demanda nacional, tampoco es frecuente priorizar el análisis de la demanda internacional frente a los ejercicios de diseño de producto turístico. Este eje pretende generar un acercamiento de los destinos a los aspectos más relevantes de la demanda, con el fin de identificar las necesidades en investigación de mercados y estructuración de mediciones que sean necesarias para la toma de decisiones de cara al turismo internacional.

70. Ingreso de visitantes internacionales no residentes al municipio: número de visitantes *internacionales no residentes* (excursionistas y turistas) que ingresan al distrito o municipio provenientes desde de su lugar de residencia u otro destino, por una duración inferior a un año y con motivos personales, profesionales o de negocios.

Evaluación

CRITERIO	PUNTAJE
El distrito o municipio **SÍ** realiza la medición del número de visitantes internacionales no residentes que recibe.	10
El distrito o municipio **EVENTUALMENTE** realiza la medición del número de visitantes internacionales no residentes que recibe (temporadas altas, ferias y eventos, otras actividades).	5
El distrito o municipio **NO** realiza medición del número de visitantes internacionales no residentes que recibe.	0

1. Visitantes internacionales no residentes hace referencia a los visitantes que ingresan al distrito o municipio provenientes del extranjero (colombianos residentes en el exterior y extranjeros no residentes), para este indicador, excursionistas y turistas.

Fuente de consulta: *Migración Colombia.*
Sistemas de información turística distritales o municipales.
Documentación oficial de la alcaldía distrital o municipal.
Cuadro de información: *escriba el número exacto de visitantes INTERNACIONALES NO RESIDENTES (excursionistas y turistas) que ingresaron al distrito o municipio en el año anterior a la implementación de esta metodología. Ejemplo: enero de 2020 a diciembre de 2020.*

71. Variación en la llegada de visitantes internacionales no residentes al distrito o municipio: la relación en porcentaje, entre el número de visitantes *internacionales no residentes* que ingresó al distrito o municipio durante el último año y el número de visitantes *internacionales no residentes* reportado en el año inmediatamente anterior.

Evaluación

CRITERIO	PUNTAJE
El distrito o municipio reporta una variación por **ENCIMA** del crecimiento o por **DEBAJO** del descenso en la llegada de visitantes extranjeros (su resultado es mejor que la base de evaluación).	10
El distrito o municipio reporta una variación **IGUAL** al crecimiento o descenso de la llegada de visitantes extranjeros (su resultado es igual que la base de evaluación).	6
El distrito o municipio reporta una variación por **DEBAJO** del crecimiento o por **ENCIMA** del descenso de la llegada de visitantes extranjeros (su resultado es peor que la base de evaluación).	2
El distrito o municipio **NO** cuenta con información suficiente para determinar la variación de la llegada de visitantes extranjeros.	0

Fuente de consulta: *Migración Colombia.*
Sistemas de Información Turística distritales o municipales.
Documentación oficial de la alcaldía distrital o municipal.
Cuadro de información: *hacer uso de la siguiente fórmula: ((número de visitantes internacionales del año 2 (2020) – número de visitantes internacionales del año 1 (2019)) /año 1 (2019)) *100*

Se toma como referencia el porcentaje de incremento o descenso de visitantes internacionales de acuerdo con las cifras de la Organización Mundial del Turismo, como valor máximo para el crecimiento o disminución del número de visitantes. Esta referencia variará según las cifras que presente la Organización Mundial del Turismo en el "Barómetro del Turismo Mundial" cada año.

72. Procedencia de los mercados internacionales potenciales: identificación del origen (países) de los visitantes internacionales (*colombianos residentes en el exterior y extranjeros no residentes*) que ingresan al distrito o municipio.

Evaluación

CRITERIO	PUNTAJE
El distrito o municipio **SÍ** identifica la procedencia de los mercados internacionales potenciales.	10

El distrito o municipio **NO** identifica la procedencia de los mercados internacionales potenciales.	0

Fuente de consulta: *Migración Colombia, sistemas de información turística distritales o municipales y documentación oficial de la alcaldía distrital o municipal.*
Cuadro de información: *escriba el texto de los TRES destinos (países) que corresponden a la procedencia de los visitantes internacionales que ingresan al distrito o municipio.*

73. Conectividad aérea internacional (porcentaje de ocupación de sillas aéreas en vuelos internacionales): hace referencia al número de asientos ocupados por pasajeros en vuelos internacionales, sobre el número de sillas disponibles para la venta. Incluye los asientos ya vendidos en una etapa de vuelo como los ocupados por pasajeros en tránsito, pero excluye los asientos que no estén realmente disponibles para el transporte de pasajeros debido a límites del peso bruto máximo de operación.

Evaluación

CRITERIO	PUNTAJE
El porcentaje de ocupación promedio en vuelos internacionales para el departamento está entre **80,1% y 100%**	10
El porcentaje de ocupación promedio en vuelos internacionales para el departamento está entre **60,1% y 80%**	8
El porcentaje de ocupación promedio en vuelos internacionales para el departamento está entre **40,1% y 60%**	6
El porcentaje de ocupación promedio en vuelos internacionales para el departamento está entre **20,1% y 40%**	4
El porcentaje de ocupación promedio en vuelos internacionales para el departamento es mayor que **0% y hasta 20%**	2
No aplica para el departamento.	5*

1. Este indicador evaluará información a nivel departamental.
2. Hace referencia a vuelos internacionales.

Fuente de consulta: *Aeronáutica Civil de Colombia. Tráfico Equipo. [Base de datos]. Corte primer trimestre 2020. Recuperado de http://www.aerocivil.gov.co/atencion/estadisticas-de-las-actividades-aeronauticas/bases-de-datos*
Base porcentaje de ocupación promedio en vuelos nacionales.
Cuadro de información: *indique el nombre del aeropuerto seleccionado como principal receptor de de vuelos internacionales con visitantes que se dirigen al distrito o municipio (entiéndase como "principal" el aeropuerto más utilizado por los turistas para llegar al distrito o municipio, aunque deban utilizar otros medios de transporte para llegar al destino).*

EVALUACIÓN DEL EJE DEMANDA INTERNACIONAL (15%)

Como resultado de la evaluación de los indicadores previamente descritos, se generará un puntaje para el eje "Demanda internacional" que será calculado realizando la división de la sumatoria del total de los criterios ya evaluados en el eje en el número total de criterios, que para este caso es **4**. El resultado será multiplicado por **15%** que corresponde al peso porcentual del eje sobre el componente de demanda.

EJE 10.
GASTO TURÍSTICO

Hace referencia al dinero que gasta el turista en el desarrollo de actividades asociadas al viaje. De acuerdo con el Departamento Administrativo Nacional de Estadísticas (DANE), incluye transporte, alimentos y bebidas, alojamiento, servicios culturales y recreacionales, souvenirs, artesanías y regalos, bienes de uso personal y otros gastos relacionados con el viaje.

Para el desarrollo turístico territorial es de gran importancia conocer el comportamiento de este indicador, entendiendo que su medición y análisis posibilitan la estructuración e implementación de estrategias para el fortalecimiento y diversificación de productos y el mejoramiento de la calidad en la prestación de los servicios; así como la comprensión del impacto de las acciones de promoción y comercialización y del comportamiento de la demanda. El trabajo de un destino enfocado hacia el incremento del gasto turístico puede generar las condiciones para que un distrito, municipio o región logre mayores beneficios económicos para las comunidades locales, favoreciendo así la sostenibilidad de la actividad.

74. **Gasto per cápita promedio diario del turista interno en el distrito o municipio:** valor en pesos colombianos relacionados con los gastos diarios de viaje donde se incluye el transporte terrestre (hacia y desde el destino), alimentos y bebidas, alojamiento, servicios culturales y recreacionales, souvenirs, artesanías y regalos, bienes de uso personal y otros gastos relacionados con el viaje (DANE, 2020).

Evaluación

CRITERIO	PUNTAJE
El gasto diario promedio del turista interno en el distrito o municipio es **SUPERIOR** al promedio nacional.	10
El gasto diario promedio del turista interno en el distrito o municipio es **IGUAL** al promedio nacional.	6
El gasto diario promedio del turista interno en el distrito o municipio es **INFERIOR** al promedio nacional.	2
El distrito o municipio **NO** realiza la medición del gasto diario promedio del turista interno.	0

1. Promedio gasto per cápita día turista interno: $70.799 de acuerdo con la información del Departamento Nacional de Estadística (DANE, 2020). Departamento Administrativo Nacional de Estadística (DANE), Boletín Técnico Encuesta de Gasto Interno en Turismo (EGIT), 26 de marzo de 2021. https://www.dane.gov.co/index.php/estadisticas-por-tema/servicios/turismo/encuesta-de-gasto-interno-en-turismo-egit

Fuente de consulta: *documentación oficial del distrito o municipio.*
Cuadro de información: *indicar la cifra de gasto promedio del turista interno, que corresponda al año inmediatamente anterior al que se implementa la metodología.*

75. **Gasto per cápita promedio diario del turista internacional en el municipio**: valor en pesos colombianos relacionados con los gastos de viaje donde se incluye el transporte internacional (hacia y desde el destino), paquete turístico, alimentos y bebidas, alojamiento, servicios culturales y de entretenimiento, tours (internos), tratamientos de salud o belleza, transporte interno en Colombia y otros gastos relacionados con el viaje (DANE, 2013).

Evaluación

CRITERIO	PUNTAJE
El gasto diario promedio del visitante internacional en el distrito o municipio es **SUPERIOR** al promedio nacional para el visitante internacional.	10
El gasto diario promedio del visitante internacional en el distrito o municipio es **IGUAL** al promedio nacional para el visitante internacional.	6
El gasto diario promedio del visitante internacional en el distrito o municipio es **INFERIOR** al promedio nacional para el visitante internacional.	2
El distrito o municipio **NO** realiza la medición del gasto diario promedio del visitante internacional.	0

1. *Promedio gasto diario por viaje del visitante internacional (receptor) $306.285 diario (DANE EVI 2013) de acuerdo con la información del Departamento Administrativo Nacional de Estadística (DANE), gasto turismo. Encuesta de Viajeros Internacionales (EVI), 2013. https://www.dane.gov.co/index.php/estadisticas-por-tema/servicios/turismo/encuesta-de-viajeros-internacionales*

Fuente de consulta: *documentación oficial del distrito o municipio.*
Cuadro de información: *indicar la cifra de gasto promedio del turista internacional, que corresponda al año inmediatamente anterior al que se implementa la metodología.*

EVALUACIÓN DEL EJE GASTO (15%)

Como resultado de la evaluación de los indicadores previamente descritos, se generará un puntaje para el eje "Gasto" que será calculado realizando la división de la sumatoria del total de los criterios ya evaluados en el eje en el número total de criterios, que para este caso es **2**. El resultado será multiplicado por **15%** que corresponde al peso porcentual del eje sobre el componente de demanda.

EJE 11.
OCUPACIÓN HOTELERA

El indicador asociado a la ocupación hotelera permite medir el comportamiento de las visitas por turismo a través de la relación entre las habitaciones ocupadas y las habitaciones disponibles en un destino. Su análisis permite comprender el impacto de las inversiones y de la ampliación de la oferta de habitaciones, así como su conexión con la llegada de turistas, la formalización y la rentabilidad del sector de alojamiento y hospedaje.

Conocer el comportamiento de este indicador y su medición y análisis posibilitan la estructuración e implementación de estrategias para el fortalecimiento empresarial, la formalización y la rentabilidad de estos establecimientos. Así mismo, da información a los municipios y distritos frente al consumo turístico y el comportamiento y preferencias de la demanda, para que desde su papel sea posible fortalecer aspectos asociados a la competitividad, infraestructura y promoción turística.

76. **Ocupación hotelera anual:** indica la proporción de ocupación de las habitaciones disponibles en un distrito o municipio. Se obtiene al dividir el número de habitaciones vendidas al año en promedio entre el número de habitaciones disponibles anualmente multiplicado por 100 (DANE, 2020).

Evaluación

CRITERIO	PUNTAJE
El distrito o municipio reporta un promedio de ocupación hotelera anual **SUPERIOR** al promedio nacional.	10
El distrito o municipio reporta un promedio de ocupación hotelera anual **IGUAL** al promedio nacional.	6
El distrito o municipio reporta un promedio de ocupación hotelera anual **INFERIOR** al promedio nacional.	2
El distrito o municipio **NO** realiza la medición de su ocupación hotelera anual.	0

Tasa de ocupación hotelera 2020: 21,18%. (COTELCO, 2021)
https://www.cotelco.org/noticias/ocupacion_2020

Fuente de consulta: *documentación oficial del distrito o municipio.*
Cuadro de información: *indicar el porcentaje anual de ocupación hotelera de su distrito o municipio.*

EVALUACIÓN DEL EJE OCUPACIÓN HOTELERA (15%)

Como resultado de la evaluación de los indicadores previamente descritos, se generará un puntaje para el eje "ocupación hotelera" que será calculado realizando la división de la sumatoria del total de los criterios ya evaluados en el eje en el número total de criterios, que para este caso es **1**. El resultado será multiplicado por **15%** que corresponde al peso porcentual del eje sobre el componente de demanda.

EJE 12.
PERNOCTACIÓN

El indicador de pernoctación permite analizar el comportamiento de las visitas por turismo a través de la medición del promedio de noches que los turistas permanecen en un establecimiento de alojamiento y hospedaje.

Conocer el comportamiento de este indicador, así como su medición y análisis, posibilita la estructuración e implementación de estrategias que permitan extender las estadías y por consiguiente, aumentar el gasto turístico.

77. Promedio de pernoctación por tipo de alojamiento y motivo de viaje: cada una de las noches que un viajero permanece o está registrado en un establecimiento de alojamiento colectivo o en un alojamiento turístico privado (DANE, 2020)

Evaluación

CRITERIO	PUNTAJE
El distrito o municipio reporta un promedio de pernoctación **SUPERIOR** al promedio nacional.	10
El distrito o municipio reporta un promedio de pernoctación **IGUAL** al promedio nacional.	6
El distrito o municipio reporta un promedio de pernoctación **INFERIOR** al promedio nacional.	2
El distrito o municipio **NO** realiza la medición del promedio de pernoctación de los visitantes.	0

1. Número de noches promedio de pernoctación año 2020: 6,5 noches
Encuesta de Gasto Interno en Turismo (EGIT) del 26 de marzo de 2021.
https://www.dane.gov.co/index.php/estadisticas-por-tema/servicios/turismo/encuesta-de-gasto-interno-en-turismo-egit

Fuente de consulta: *documentación oficial del distrito o municipio.*

Cuadro de información: *indicar el número promedio de noches de pernoctación de los turistas en el distrito o municipio para el año inmediatamente anterior a la implementación de esta metodología.*

EVALUACIÓN DEL EJE PERNOCTACIÓN (15%)

Como resultado de la evaluación de los indicadores previamente descritos, se generará un puntaje para el eje "Pernoctación" que será calculado realizando la división de la sumatoria del total de los criterios ya evaluados en el eje en el número total de criterios, que para este caso es **1**. El resultado será multiplicado por **15%** que corresponde al peso porcentual del eje sobre el componente de demanda.

EJE 13.
PRESENCIA DIGITAL

La presencia digital de un destino hace referencia a su visibilidad en internet, bien sea a través de una página web, redes sociales, resultados en motores de búsqueda y anuncios o cualquier otro formato pago. Para esta metodología, el eje pretende comprender la visibilidad de un distrito o municipio en el contexto de viajes y turismo, dando una idea de la frecuencia y temporalidad en la que se realizan las búsquedas.

El análisis de estos indicadores permitirá identificar los intereses de potenciales turistas extranjeros y nacionales frente a la oferta de viajes y turismo de un distrito o municipio. Así mismo, será uno de los primeros insumos para identificar el nivel de presencia digital de un destino y las posibilidades de mejora frente a su potencial.

78. Presencia digital <u>mundial</u> del distrito o municipio en la plataforma Google Trends: permite conocer y analizar las tendencias de búsqueda, la popularidad y la evolución de términos o palabras clave a nivel mundial. Para este ejercicio se seleccionará el filtro de la categoría "viajes" o "travel" y "todo el mundo" o "worldwide" en la plataforma de Google Trends.

Evaluación

CRITERIO	PUNTAJE
El distrito o municipio presenta una **POPULARIDAD ALTA** en el interés de búsqueda entre 66,8 y hasta 100 en Google Trends, en la categoría de "viajes" por el criterio de búsqueda "todo el mundo".	10
El distrito o municipio presenta una **POPULARIDAD MEDIA** en el interés de búsqueda entre 33,1 y hasta 66,7 en Google Trends, en la categoría de "viajes" por el criterio de búsqueda "todo el mundo".	5
El distrito o municipio presenta una **POPULARIDAD BAJA** en el interés de búsqueda mayor que 0 y hasta 33 en Google Trends, en la categoría de "viajes" por el criterio de búsqueda "todo el mundo".	0

Fuente de consulta: *Google Trends, https://trends.google.es*
Cuadro de información: *indique el valor del promedio ponderado anual (Ejemplo: 1 de abril de 2020 a 1 de abril de 2021) del interés de búsqueda en Google Trends del distrito o municipio en la categoría de "viajes" en el criterio de búsqueda de "todo el mundo".*
Indicaciones de uso de la plataforma:
1. Para este indicador se tomará la información del último año (Ejemplo: 1 de abril de 2020 - 1 de abril de 2021).
2. Para realizar la medición será necesario realizar el siguiente proceso:
a. Ingrese a la plataforma de Google Trends y en el buscador escriba el nombre de su municipio asegurándose que sea su distrito o municipio.
b. Seleccione las opciones: (1) "Todo el mundo" (Worldwide), (2) "últimos 12 meses" (past 12 months), (3) "Viajes" (travel) y (4) "búsqueda web" (web search).
c. Descargue el archivo de Excel resultado de su búsqueda y elimine las fechas en cada fila, con el propósito de conservar el promedio de búsqueda semanal.
d. Realice el promedio de los 52 datos con el fin de conocer la popularidad de búsquedas de su distrito o municipio.

79. Presencia digital <u>nacional</u> del distrito o municipio en la plataforma Google Trends: permite conocer y analizar las tendencias de búsqueda, la popularidad y la evolución de términos o palabras clave a nivel nacional. Para este ejercicio se seleccionará el filtro de la categoría "viajes" o "travel" y "Colombia".

Evaluación

CRITERIO	PUNTAJE
El municipio presenta una **POPULARIDAD ALTA** en el interés de búsqueda entre 66,8 y hasta 100 en Google Trends, en la categoría de "viajes" por el criterio de búsqueda de "Colombia".	10
El municipio presenta una **POPULARIDAD MEDIA** en el interés de búsqueda entre 33,1 y hasta 66,7 en Google Trends, en la categoría de "viajes" por el criterio de búsqueda de "Colombia".	5
El municipio presenta una **POPULARIDAD BAJA** en el interés de búsqueda mayor que 0 y hasta 33 en Google Trends, en la categoría de "viajes" por el criterio de búsqueda de "Colombia".	0

Fuente de consulta: *Google Trends, https://trends.google.es*
Cuadro de información: *indique el valor del promedio ponderado anual (Ejemplo: 1 de abril de 2020 a 1 de abril de 2021) del interés de búsqueda en Google Trends del distrito o municipio en la categoría de "viajes" en el criterio de búsqueda de "todo el mundo".*
Indicaciones de uso de la plataforma:
1. Para este indicador se tomará la información del último año (Ejemplo: 1 de abril de 2020 - 1 de abril de 2021).
2. Para realizar la medición será necesario realizar el siguiente proceso:
a. Ingrese a la plataforma de Google Trends y en el buscador escriba el nombre de su municipio asegurándose que sea su distrito o municipio.
b. Seleccione las opciones: (1) "Colombia" (2) "últimos 12 meses" (past 12 months), (3) "Viajes" (travel) y (4) "búsqueda web" (web search).
c. Descargue el archivo de Excel resultado de su búsqueda y elimine las fechas en cada fila, con el propósito de conservar el promedio de búsqueda semanal.
d. Realice el promedio de los 52 datos con el fin de conocer la popularidad de búsquedas de su distrito o municipio.

EVALUACIÓN DEL EJE PRESENCIA DIGITAL (10%)

Como resultado de la evaluación de los indicadores previamente descritos, se generará un puntaje para el eje "Presencia digital" que será calculado realizando la división de la sumatoria del total de los criterios ya evaluados en el eje en el número total de criterios, que para este caso es **2**. El resultado será multiplicado por **10%** que corresponde al peso porcentual del eje sobre el componente de demanda.

EJE 14.
SATISFACCIÓN DE LOS VIAJEROS

La medición de la satisfacción de los viajeros permite analizar el resultado de su experiencia en un destino. La importancia de este indicador radica en la necesidad de conocer cuáles son los aspectos que impactan de forma positiva o negativa el desarrollo de los desplazamiento por turismo, entendiendo que esto puede beneficiar o afectar un distrito o municipio en términos de sostenibilidad económica y social.

El análisis de este indicador permitirá identificar los elementos que son bien catalogados por el turista y que el distrito o municipio debe conservar y fortalecer. Así mismo, permitirá identificar los aspectos de mejora que deben ser atendidos de manera prioritaria, con el fin de garantizar una experiencia satisfactoria de cara al visitante.

80. Satisfacción de los viajeros: define el nivel de satisfacción de los viajeros frente a los atractivos, servicios, productos y experiencias turísticas del distrito o municipio.

CRITERIO	PUNTAJE
El distrito o municipio **SÍ** mide sistemáticamente la satisfacción de los viajeros.	10
El distrito o municipio **NO** mide sistemáticamente la satisfacción de los viajeros.	0

Fuente de consulta: *encuestas e informes distritales o municipales de la autoridad de turismo sobre satisfacción de los viajeros.*

EVALUACIÓN DEL EJE SATISFACCIÓN DE LOS VIAJEROS (10%)

Como resultado de la evaluación de los indicadores previamente descritos, se generará un puntaje para el eje "Satisfacción de los viajeros" que será calculado realizando la división de la sumatoria del total de los criterios ya evaluados en el eje en el número total de criterios, que para este caso es **1**. El resultado será multiplicado por **10%** que corresponde al peso porcentual del eje sobre el componente de demanda.

REFERENCIAS BIBLIOGRÁFICAS

Aeronáutica Civil. (2020). Bases de datos. Recuperado de: http://www.aerocivil.gov.co/atencion/estadisticas-de-las-actividades-aeronauticas/bases-de-datos

Corte Constitucional de Colombia. (2008). Sentencia C – 064 de 2008. Bogotá, Colombia.

DANE. (2021). Boletín Técnico Encuesta de Gasto Interno en Turismo (EGIT), I trimestre de 2020 (2 de octubre de 2020). Recuperado de: https://www.dane.gov.co/index.php/estadisticas-por-tema/servicios/turismo/encuesta-de-gasto-interno-en-turismo-egit

DANE. (2013) Encuesta de Viajeros Internacionales (EVI), (diciembre de 2013). Recuperado de: https://www.dane.gov.co/index.php/estadisticas-por-tema/servicios/turismo/encuesta-de-gasto-interno-en-turismo-egit

DANE. (2020). Visor de Turismo, conceptos básicos. https://sitios.dane.gov.co/turismo/#!/

Decreto 348 de 2015. Ministerio de Transporte, Bogotá, Colombia, 25 de febrero de 2015.

Decreto 2106 de 2019. Departamento Administrativo de la Función Pública, Bogotá, Colombia, 22 de noviembre de 2019.

Decreto 2762 de 2001. Ministerio de Transporte, Bogotá, Colombia, 27 de diciembre de 2001.

INNpulsa. (2020). *Innpulsa Colombia*. Recuperado de: www.innpulsacolombia.com

Ley 115 de 1994. Congreso de la República de Colombia, Bogotá, Colombia, 8 de febrero de 1994.

Ley 1185 de 2008. Congreso de la República de Colombia, Bogotá, Colombia, 12 de marzo de 2008.

Ley 1558 de 2012. Congreso de la República de Colombia, Bogotá, Colombia, 10 de julio de 2012.

Ley 300 de 1996. Congreso de la República de Colombia, Bogotá, Colombia, 26 de julio de 1996.

Ley 599 de 2000. Congreso de la República de Colombia, Bogotá, Colombia, 24 de julio de 2000.

Ley 70 de 1993. Congreso de la República de Colombia. Quibdó, Colombia. 27 de agosto de 1993.

Ley 769 de 2002. Congreso de la República de Colombia, Bogotá, Colombia, 6 de agosto de 2002.

Ley 1618 de 2013. Congreso de la República de Colombia, Bogotá, Colombia, 27 de febrero de 2002.

Ministerio de Comercio, Industria y Turismo. (2019). Caja de Herramientas para el sector turístico. Recuperado de: https://www.mincit.gov.co/getattachment/minturismo/caja-de-herramientas/caja-de-herramientas/turismofin.pdf.aspx

Ministerio de Comercio, Industria y Turismo. (2015). *Manual de buenas prácticas para la prevención de la ESCNNA en viajes y turismo*. Bogotá, Colombia: Ministerio de Comercio, Industria y Turismo.

Ministerio de Cultura. (2020). *Bienes de Interés Cultural del Ámbito Nacional*. Recuperado de: https://www.mincultura.gov.co/areas/patrimonio/unesco/bicnal/Paginas/default.aspx

Ministerio de las Tecnologías de la Información y las Comunicaciones. (2020). *Boletín servicio acceso fijo a internet en Colombia*. Bogotá, Colombia: Ministerio de las Tecnologías de la Información y las Comunicaciones.

Resolución 3067 de 2011. Comisión de Regulación de Comunicaciones, Bogotá, Colombia, 18 de mayo de 2011.

Decreto 1651 de 2019. Presidencia de la República, Bogotá, Colombia, 11 de septiembre de 2019.

Resolución 01092 de 2007. Unidad Administrativa Especial de Aeronáutica Civil. Recuperado de: http://www.aerocivil.gov.co/normatividad/Resoluciones%20TA%202007/01092%20del%2013-03-07.pdf

Superintendencia de Servicios Públicos. (2020). Indicadores "cobertura de acueducto", "cobertura de alcantarillado", "cobertura de servicio de aseo" y "cobertura de servicio de energía eléctrica".

Organización Mundial del Turismo – OMT. (2005). *Indicadores de desarrollo sostenible para los destinos turísticos. Guía práctica*. Madrid, España: Organización Mundial del Turismo.

Organización Internacional del Turismo – OIT. (2020). *Mano de obra, empleo, desempleo y movilidad. Empleo informal*. Recuperado de: https://www.oitcinterfor.org/taxonomy/term/3366#:~:text=Incluye%20todo%20trabajo%20remunerado%20(p,ej.&text=Los%20trabajadores%20informales%20no%20cuentan,o%20representaci%C3%B3n%20de%20los%20trabajadores

Policía Nacional de Colombia. (2017). *Dirección Nacional de Escuelas. Tráfico de Fauna*. Recuperado de: http://www.aecidcf.org.co/Ponencias/2017/octubre/MI231017-2/13.Trafico_fauna.pdf

Superintendencia de Industria y Comercio – SIC. (2020). *Consumidor turista*. Recuperado de: https://www.sic.gov.co/consumidor-turista

BIBLIOGRAFÍA

Boston Consulting Group. (1973). Matriz BCG.

Boullón, R. (1986). Planificación del espacio turístico. México D.F., México: Editorial Trillas.

Butler, R. (1989). Ciclo de vida de los destinos turísticos.

CEPTUR. (2019) Índice de Competitividad Turística Regional de Colombia – ICTRC. Departamentos. Bogotá, Colombia: Estrategik-mente.

CEPTUR. (2019) Índice de Competitividad Turística Regional de Colombia – ICTRC. Municipios y ciudades capitales. Bogotá, Colombia: Estrategik-mente.

World Economic Forum. (2019). Travel & Tourism Competitiveness Index.